CÓDIGO DE PLANEAMIENTO URBANO RURAL DE LA CIUDAD DE PLOTTIER

DOCUMENTO DE ACTUALIZACIÓN

SUBSECRETARÍA DE OBRAS,
PLANEAMIENTO Y CATASTRO

ENTE DESARROLLO
ECONÓMICO DE PLOTTIER
(EDEP)

MUNICIPALIDAD DE PLOTTIER
PROVINCIA DEL NEUQUÉN
MAYO 2014

Contenidos

Capítulo I: Disposiciones generales

Capítulo II: Procedimientos de Factibilidad Territorial Ambiental

Capítulo III: Zonas Urbanas – Parámetros Urbanísticos

Capítulo IV: Zonas rurales y Extraurbanas - Usos de Suelo

Anexo: Plano Corredores Urbanos
Plano Corredores de Vinculación Urbano Rural - Zona Este
Plano Corredores de Vinculación Urbano Rural - Zona Oeste
Plano Áreas de Zonificación Rural – Extraurbana
Plano Polígono Urbano Proyectado
Plano Áreas de Reserva para Crecimiento Urbano
Plano Áreas de Zonificación Urbana

Resumen metodológico

La actualización del Código de Planeamiento Urbano Rural de Plottier (Ord. N°2.315/04), se fundamenta en la necesidad de adaptar la actual normativa de planeamiento a los cambios que ha experimentado el ejido municipal desde el año 2.004 al presente, período en el que se acentuó una fuerte ocupación del territorio con procesos de urbanización, junto a la aparición de nuevas formas de uso del suelo que no se presentaban en períodos anteriores de la historia local.
Esta dinámica requiere que el Estado Municipal disponga de herramientas de planificación y gestión que posibiliten un abordaje adecuado de estos procesos, teniendo como premisa los postulados de la Carta Orgánica Municipal y la Carta Ambiental de Plottier, con la finalidad de concretar un desarrollo sustentable de los espacios urbanos y rurales, preservando la calidad ambiental y exaltando los atributos identitarios de la ciudad.
El presente documento es el resultado de un proceso de estudio, en el cual se utilizó una metodología de análisis territorial – ambiental, que se desarrollo en distintas etapas.
En la instancia de diagnóstico, se realizó una caracterización del ejido y su situación respecto a la expansión urbana y los usos de suelo urbanos y rurales, así como la inserción de la ciudad en el marco del desarrollo regional y su interacción con Neuquén Capital y otros centros urbanos.
Posteriormente se examinó la ordenanza actual de planeamiento, a los efectos de identificar los aspectos que requerían actualización e incorporación de nuevos parámetros.
A partir de estos análisis se redefinieron las zonas urbanas y rurales, determinándose para cada una de ellas los parámetros urbanísticos y de uso del suelo. Se crearon las "áreas de reserva para crecimiento urbano" definiéndose un "polígono urbano proyectado", a efectos de determinar los límites dentro de los cuales debe crecer la ciudad en los próximos años, salvaguardando de esa forma los espacios necesarios para las actividades productivas rurales. Se incorporaron además nuevas herramientas de ordenamiento, tales como los convenios urbanísticos, la definición de corredores urbanos, los procedimientos de factibilidad territorial – ambiental, la protección del oasis irrigado y la incorporación del arbolado urbano como elemento integrador del paisaje.
Resulta importante destacar, que durante el desarrollo de las distintas actividades y reuniones de trabajo que dieron como resultado el documento de actualización, se sostuvo la idea y la visión de Plottier como una ciudad inclusiva y equilibrada, que pueda ofrecer a sus habitantes una identidad urbana distintiva, caracterizada por edificaciones de baja altura, baja densidad poblacional, veredas y calles amplias, espacios verdes abundantes y respeto por el entorno natural y los elementos que conformaron el ambiente productivo rural preexistente.

Plottier, año 2014.-

CAPITULO I

DISPOSICIONES GENERALES

1. DEFINICIONES Y TERMINOLOGÍA APLICADA

1.1. PARÁMETRO URBANÍSTICO: Indicador que se utiliza para determinar las características de ocupación del espacio y los usos de suelo de una determinada zona o corredor urbano.

1.2. ZONIFICACIÓN TERRITORIAL: Definición de zonas urbanas, rurales y extraurbanas, determinadas en función de capacidades, potencialidades y restricciones del territorio. Cada zona posee indicadores que regulan su desarrollo y los usos de suelo que puede albergar. Se visualiza por medio de un plano de zonificación territorial.

1.3 ZONA URBANA (ZU): Toda aquella zona comprendida dentro de la zonificación urbana, en la cual predominan usos de suelo residenciales, comerciales y de servicios, incluyendo las actividades e infraestructura que requiere el ámbito territorial urbano. Cada zona urbana se encuentra caracterizada por parámetros urbanísticos y usos de suelo específicos.

1.4. POLÍGONO URBANO PROYECTADO: Espacio territorial comprendido por el conjunto de zonas urbanas del ejido municipal, y las áreas de crecimiento urbano proyectadas. Dentro del mismo se considera prioritario el desarrollo del equipamiento e infraestructura urbana.

1.5. ZONA RURAL – EXTRAURBANA (ZR): Toda aquella zona comprendida fuera de la zonificación urbana, en la cual no se encuentra permitido el desarrollo del uso residencial urbano. Se caracteriza por el predominio de actividades agropecuarias, industriales o de servicios, de acuerdo a la zona de la que se trate. El uso residencial es de carácter disperso. Cada zona rural se encuentra caracterizada por superficies
mínimas de fraccionamiento y usos de suelo permitidos. Es el ámbito dentro del cual se considera prioritario el desarrollo del equipamiento e infraestructura rural y extraurbana.

1.6. AREA DE RESERVA PARA CRECIMIENTO URBANO (ARCU): Constituye la única área del ejido municipal destinada a la expansión urbana, dentro de la cual se permitirá el desarrollo de proyectos de urbanización, sujetos a convenio urbanístico y a los parámetros urbanísticos previstos para el sector. Toda parcela ubicada dentro de la ARCU que no se encuentre incorporada a un proyecto de urbanización se considerará como parcela "rural – extraurbana", y se halará

sujeta a los parámetros de subdivisión y usos previstos para la ZR que la comprende.

1.7. CORREDOR URBANO: Espacio urbano de carácter lineal, que se extiende a lo largo de una avenida o calle principal. Se caracteriza por el predominio de Código de Planeamiento Urbano Rural de Plottier – Actualización 2013 actividades comerciales, equipamientos y/o servicios urbanos, con los cuales se pretende dotar a las zonas urbanas aledañas.

1.8. CORREDOR DE VINCULACIÓN URBANO RURAL: Corredor definido en espacios aledaños a la Ruta Nac. 22, vías férreas, canal principal de riego o caminos rurales, que permite generar conectividad espacial del territorio y vincular el espacio urbano con la ruralidad. Posibilita la creación de redes de espacios públicos conectados por medios de ciclovías o sendas peatonales.

1.9 URBANIZACIÓN RURAL: Se denomina de esta manera a todo emprendimiento urbanístico, ubicado fuera de la zona urbana o área de reserva para crecimiento urbano.

1.10. CLASIFICACIÓN DE USOS DE SUELO:

1.10.1. USOS DE SUELO PRINCIPALES: Constituyen los usos de suelo dominantes que caracterizan el área (comercial, residencial, de servicios, etc.).

1.10.2. USOS DE SUELO COMPLEMENTARIOS: Son usos que acompañan a los usos principales, y deben adaptarse a la dinámica de la zona.

1.10.3. USOS DE SUELO CONDICIONADOS: Son usos de suelo cuya aprobación requiere ineludiblemente de estudios previos, debiendo demostrar su compatibilidad con el entorno y los parámetros de zonificación establecidos para el área.

1.11. PROCEDIMIENTO EIA: Refiere al procedimiento de Evaluación de Impacto Ambiental previsto en la Ley Provincial 1875, Decreto Reglamentario N° 2.656/99, Ordenanza Municipal 1899/00.

1.12 FACTIBILIDAD TERRITORIAL AMBIENTAL: FTA: Refiere al procedimiento de Factibilidad Territorial – Ambiental que se encuentra detallado en el Capítulo II.

1.13. ESTUDIO DE IMPACTO AMBIENTAL (EsIA): Documento que se elabora a efectos de evaluar los impactos de obras o actividades humanas de mayor incidencia ambiental (ver listado no taxativo Decreto Reglamentario N° 2.656/99)

1.14. INFORME AMBIENTAL (IA): Documento que se elabora a efectos de evaluar los impactos de obras o actividades humanas de menor incidencia ambiental (ver listado no taxativo Decreto Reglamentario N° 2.656/99)

1.15. AUDITORIA AMBIENTAL (AA): Documento que se elabora a efectos de evaluar los impactos de obras o actividades humanas que se encuentran en funcionamiento, con anterioridad a la puesta en vigencia del procedimiento EIA.

1.16. INFORME DE IMPACTO URBANO AMBIENTAL (IIUA): Refiere a los términos de referencia específicos para proyectos urbanísticos de baja incidencia ambiental, detallados en el Capítulo II.

1.17. ESTUDIO DE IMPACTO URBANO AMBIENTAL (EIUA): Refiere a los términos de referencia específicos para proyectos urbanísticos de alta incidencia ambiental, detallados en el Capítulo II.

2. FACTIBILIDAD DE USO DE SUELO:

La autorización de usos de suelo para todos los proyectos urbanísticos, obras nuevas y actividades económicas dentro del ejido municipal de Plottier, se regirá de acuerdo a las disposiciones establecidas en el Capítulo II "Procedimientos de Factibilidad Territorial – Ambiental".

3. ESPACIOS VERDES (EV):

A los efectos del presente documento, se consideran espacios verdes a aquellos espacios urbanos en los que predomina la vegetación y el paisaje, cuya función principal consiste en servir a la integración y el esparcimiento de la comunidad y contribuir a una mejor calidad ambiental urbana.

3.1. CONDICIONES DE DISEÑO Y EQUIPAMIENTO QUE DEBEN CUMPLIR LOS ESPACIOS VERDES INCLUIDOS EN LOS PROYECTOS URBANÍSTICOS:

3.1.1. Los EV tendrán una superficie no menor al10% de la superficie de la parcela; para el cálculo del mencionado porcentaje, se excluirá la superficie afectada a calles.

3.1.2. Los EV serán entregados al domino municipal con proyecto de forestación y de parquizacion.

3.1.3. La ubicación y configuración de la o las parcelas destinadas a EV, estará sujeta a los objetivos y necesidades de ordenamiento territorial, siendo facultad de la autoridad municipal su determinación, en la instancia de visado preliminar. En tal sentido, los EV tendrán que ubicarse en espacios interiores centrales del futuro barrio, salvo que exista la posibilidad de generar un EV de mayor dimensiones, anexando el correspondiente a un proyecto urbanístico aledaño.

3.1.4. Todo espacio de parquización lineal, llámese boulevard, tendrá un ancho mínimo de parquización de 3,5 mts. La superficie afectada a estos espacios no

será en ningún caso computada como espacio verde.

3.1.5. Los predios destinados a EV deberán tener una morfología rectangular, con una superficie mínima de 6.000 mts.2.; los lados no serán inferiores a los 60 mts. de longitud.

4. ARBOLADO URBANO

Será obligatorio para todo proyecto urbanístico de cualquier índole, que no se encuentre en la zona ribereña, contemplar el arbolado urbano implantado en veredas. A tal efecto, en la etapa de visado definitivo del loteo se deberá presentar un proyecto de arbolado urbano, de acuerdo a las especificaciones que figuran en el Anexo I del presente.

5. RESERVAS FISCALES

La superficie afectada a reserva fiscal, será de un 5 % de la superficie de la parcela de origen, según título de propiedad. La determinación de la ubicación de la/las reserva/s fiscal/es será facultad de la autoridad municipal, lo cual se resolverá en la instancia de visado preliminar.

6. DENSIDAD HABITACIONAL NETA:

6.1. Es la relación entre el número de habitantes y la superficie del inmueble. Se considerarán para el cálculo de densidad habitacional, los siguientes valores: 4,5 habitantes / vivienda.

6.2. Con excepción de las zonas urbanas R1 Especial, R1, R2 (en el polígono centro) y os corredores urbanos que incorporen sus parámetros urbanísticos, toda zona que admita la actividad comercial aplicará para locales comerciales la siguiente densidad habitacional: 4,5 habitantes / unidad comercial.

7. PRESERVACION DE OASIS DE RIEGO:

Con el propósito de proteger el oasis irrigado, evitar la profundización de los procesos de deterioro que ha sufrido debido a la expansión urbana, y potenciar sus atributos histórico-culturales, ecológicos y paisajísticos, se implementarán las siguientes medidas:

7.1. Se promoverá la creación de reservas urbanas que permitan salvaguardar porciones del oasis irrigado, como muestras del patrimonio natural y reservorios de biodiversidad existente en la región.

7.2. Se realizarán acuerdos entre la municipalidad y los organismos

provinciales, en aquellos aspectos concernientes a la obliga ión de mantenimiento de los oasis irrigados.

7.3. Se propondrá el Reempadronamiento de los nuevos usuarios urbanos, en el Registro provincial de regantes que administra la Dirección provincial de Recursos Hídricos, bajo la figura de "productores de servicios ambientales", a efectos de evitar la desafectación de los canales de riego y desagüe y la conservación del arbolado existente que acompaña sus trazas.

7.4. En las zonas en las que en la parcela a urbanizar o afectar a algún proyecto económico, existan elementos típicos de la zona rural preexistente tales como: forestación perimetral, caminos, canales de riego y desagües, obras de arte y/o elementos arquitectónicos identitarios, todo proyecto deberá respetar los elementos citados, e integrarlos al diseño. El Informe de Impacto Urbano Ambiental deberá incluir el relevamiento y descripción detallada de los mismos, su puesta en valor y las premisas bajo las que se integrarán al proyecto de urbanización.

7.5. Dentro de cada parcela se deberá respetar al entorno natural, protegiendo y conservando las cortinas de álamos. En el caso que se deba reemplazar la vegetación existente, por razones de estado sanitario, antigüedad y/o seguridad pública, se podrá reemplazar, por la misma especie u otras nuevas especies, si el proyecto así lo amerita,para lo cual deberá con la autorización del área municipal competente.

7.6 Se deberá mantener la red de canales de riego y drenaje existente; en caso de ser necesaria alguna modificación de su traza o desafectación, la misma deberá contar con la previa autorización escrita del Organismo provincial competente en la materia, y garantizarse el libre escurrimiento del agua sin afectar las zonas que ahora se sirven.

8. TRAMITACION DE LOS PROYECTOS URBANISTICOS

La tramitación de los proyectos urbanísticos se desarrollará de acuerdo a las pautas fijadas en el capítulo II de la presente (Factibilidad Territorial Ambiental), y las disposiciones vigentes en la Ord. N° 1.913/00, sobre la cual se realizan las siguientes modificaciones:

8.1. El período de validez del diseño preliminar fijado en el artículo 11°, será de ciento ochenta (180) días.

8.2. Se deja sin efecto el inciso "d" del Artículo 21°.

8.3. Se dejan sin efecto las disposiciones de los artículos 43°, 44° Y 46° relativas a espacios verdes y reserva fiscal.

8.4. En lo referido al articulo 73° "vencimiento de las actuaciones", la autoridad de aplicación tendrá un plazo de treinta (30) días a partir de la fecha de ingreso del expediente.

9. FLEXIBILIDAD DE PARÁMETROS URBANÍSTICOS

9.1. En proyectos urbanísticos abiertos o cerrados, y siempre que existan argumentos técnicos razonables, se aceptará que hasta el 15% del total de lotes proyectados no cumplan las dimensiones mínimas de superficie y frentes previstos para la zona, pudiendo los mismos tener valores hasta el 15% menor a los establecidos.

9.2. Respecto de los demás parámetros urbanísticos, se aceptará una tolerancia general del 10 % en más o en menos respecto de los valores permitidos para la zona, siempre que existan argumentos técnicos que así lo justifiquen.

10. LÍMITES ENTRE ZONAS URBANAS

En los casos en los que el municipio lo considere factible, y salvo que las necesidades
de ordenamiento urbano indiquen la conveniencia de establecer un "borde" que diferencie calle de por medio dos zonas urbanas, los lotes frentistas a una zona urbana adyacente distinta, podrán asumir los parámetros urbanísticos de esta última, a efectos de que el pasaje de una zona a otra opere de forma gradual.

11. REDISTRIBUCIÓN PARCELARIA

En caso de que se genere una redistribución parcelaria entre dos o más lotes, donde la cantidad de parcelas resultantes es igual a la cantidad de parcelas de origen, se permitirá una reducción en las dimensiones de frente y superficie mínima de hasta un 15 %, respecto de los valores correspondientes a la zona urbana donde se ubiquen los lotes.

12. URBANIZACIONES EN ZONA RURAL

Los parámetros urbanísticos de proyectos aprobados por norma de excepción a la Ordenanza N° 2.315/04, ubicados en zonas rurales o extraurbanas (según la zonificación establecida en la presente), serán determinados por el municipio en función de las necesidades del ordenamiento territorial, y las posibilidades de acceso
a equipamientos y servicios existentes en el área.

13. CAMBIO DE SITUACIÓN DE PARCELAS RURALES

Las parcelas ubicadas en zona rural, que a partir de la puesta en vigencia de la presente actualización pasen a formar parte del área denominada "Área de Reserva para Expansión Urbana", y se encuentren efectivamente desarrollando actividades económicas propias de la zona rural, no estarán obligadas a cambiar el uso de suelo
rural actual, ni asumirán obligaciones tributaras municipales propias de la zona urbana. El carácter de "parcela en producción", que comprende a las tierras antes mencionadas, será certificado por el Ente de Desarrollo Económico de Plottier.

14. AREAS PROTEGIDAS

14.1. Se creará el Sistema Municipal de Áreas Protegidas de Plottier, con el fin de generar una norma marco que permita la conservación de los distintos ecosistemas que se encuentran dentro del ejido de la ciudad, considerando la importancia de la preservación de las zonas ecológicamente sensibles como lo son el frente de bardas y la zona ribereña.

4.2. La factibilidad para el desarrollo de un determinado uso de suelo, dentro de las áreas protegidas actuales y futuras, se regirá de acuerdo a los parámetros de uso que se establezcan en los planes de manejo respectivos.

15. CONVENIOS URBANÍSTICOS

15.1. Se denomina Convenio Urbanístico a la acción administrativa concertada que supone la autorización para personas físicas o jurídicas, públicas o privadas, con el fin de cambiar el uso del suelo y/o sus correspondientes parámetros urbanísticos, por proyectos y ejecución de obras de infraestructura y/o equipamiento público, que generen mejores condiciones de vida a los vecinos de la ciudad de Plottier.
Estos convenios, implican el desarrollo por parte del emprendedor de el/los proyectos y la ejecución de la/las obras de infraestructura y/o equipamiento público concertados con la Autoridad de Aplicación del Código de Planeamiento Urbano Rural de la ciudad de Plottier que no necesariamente se encuentren contiguas al emprendimiento en evaluación.

15.2. Todos los convenios se suscribirán en compensación:

- Por cambios de parámetros urbanísticos, o
- Por cambio de usos del suelo en el área de reserva para expansión urbana, o
- Provisión de nueva infraestructura o mejora de la misma por inversión pública.

Se priorizará el mayor beneficio para la comunidad de la ciudad de Plottier, estando enmarcados en las directrices generales del planeamiento local, así como las necesidades de obras y/o equipamientos, que surjan del análisis de la Subsecretaría de Obras, Planeamiento y Catastro u organismo que en el futuro lo suceda, quien constituye la autoridad de aplicación del presente código.

15.3. Se identifican en este documento dos tipos de Convenios Urbanísticos factibles de desarrollar:

a. Convenio Urbanístico por cambio de uso del suelo: Se podrá concertar este tipo de convenio, en aquellos casos en los que el emprendedor posee un predio ubicado dentro del Área de Reserva para Crecimiento Urbano y solicita autorización para el cambio de uso del suelo, con el fin de desarrollar un emprendimiento urbanístico.
b. Convenio Urbanístico por cambio de parámetros urbanísticos: Se podrán concertar, en aquellos casos en los que un emprendedor cuyo predio se encuentra dentro de una determinada zona urbana, solicita autorización para el cambio de parámetros urbanísticos que rigen dicha parcela (FOT, FOS, alturas, retiros, etc.). Los convenios por cambio de parámetros urbanísticos serán de aplicación única, por lo que una zona urbana afectada por este tipo de convenio, no podrá ser objeto de un nuevo convenio a futuro.

15.4. Los convenios Urbanísticos, tanto en el caso del ítem a) como en el ítem b), podrán aplicarse por única vez sobre la misma superficie territorial, inhabilitando a la misma a ser objeto de convenios a futuro.

15.5. Como máximo, se permitirá únicamente el cambio de parámetros urbanísticos a la zona urbana inmediata superior, en cuanto a densidad demográfica y superficies edificables permitidas. En el caso de la zona urbana R1 Especial, los proyectos que soliciten el cambio de parámetros urbanísticos serán objeto de evaluación por parte de la autoridad de aplicación, a efectos de determinar si resultan factibles en términos urbanísticos, ambientales y de infraestructura, no pudiendo en ningún caso exceder una altura máxima de 24 metros (Planta baja + 6 niveles).

15.6. Únicamente serán objeto de convenio urbanístico, aquellos proyectos que demuestren un impacto positivo trascendente para el desarrollo urbano de la ciudad, y contribuyan a fortalecer la identidad urbana, como así también los atributos paisajísticos, históricos y culturales de la ciudad y su entorno. Para tal fin se evaluará si las propuestas contemplan suficientes cantidades de suelo a ceder en concepto de:

• Equipamiento urbano (para futuros establecimientos educativos, de salud y otros fines públicos y comunitarios).

• Espacio público (sistema jerárquico de accesos a través de calles, avenidas, etc., calidad urbana en forma de plazas, plazoletas, arbolado).
• Parques, parques lineales y otros espacios verdes.
• Los demás aportes que fomenten la cohesión sociocultural de Plottier.

15.7. No podrán ser objeto de convenio urbanístico, aquellos proyectos que afecten una superficie total, menor a los 5.000 metros cuadrados.

15.8. El convenio deberá suscribirse bajo criterios de proporcionalidad, y estar orientado a satisfacer el bienestar público, asegurando las funciones urbanas a largo plazo, y garantizando un equilibrio entre cargas y beneficios para los actores afectados.

15.9. El solicitante podrá cumplir sus compromisos en las siguientes formas:

• Cesión de terrenos a favor del bien público y del Banco de Tierras Municipales.
• Ejecución de obras o puesta en valor de elementos de infraestructura pública y/o equipamiento público en los sectores urbanos o rurales, que la autoridad de aplicación determine en función del planeamiento local.
• Aportes en forma de dinero al Fondo Municipal de Desarrollo Urbano Rural.
Los detalles de cada caso se acuerdan entre el solicitante y la autoridad de aplicación.

15.10. En caso de que la compensación propuesta por el solicitante en el marco de un convenio urbanístico, se concrete dentro del predio original afectado al proyecto, todos los elementos que se definan como compensación, se entenderán como adicionales al cumplimiento de las exigencias que la normativa establece, en cuanto a la ejecución de obras y provisión de infraestructura técnica del predio.

15.11. DISPOSICIONES GENERALES PARA LA APLICACIÓN DE CONVENIOS URBANISTICOS:

a) Cada convenio urbanístico a concertar, deberá ser previamente analizado por la autoridad de aplicación del presente código.
b) Los aspectos centrales del convenio urbanístico en evaluación, serán objeto de la aplicación de un sistema de consulta pública no vinculante, a efectos de relevar las observaciones y perspectivas de la comunidad, y asimismo dimensionar en términos sociales, los beneficios que el convenio generará para el mejoramiento general de la ciudad.
c) Una vez determinada la viabilidad del convenio urbanístico en evaluación, se fijarán los términos, cláusulas, tiempos y todo lo concerniente al tratamiento legal del mismo y su redacción final, siendo el documento puesto a consideración del Ejecutivo municipal o el organismo que este decida, a efectos de verificar que se encuentre debidamente encuadrado en el marco normativo vigente.

d) Cada convenio urbanístico deberá contar con el expreso aval del Intendente Municipal, quien firmará el mismo junto con el funcionario/a que se encuentre a cargo de la Subsecretaría de Obras, Planeamiento y Catastro de la Municipalidad de Plottier o el organismo que a esta la reemplace en el futuro por decisión del Ejecutivo Municipal.
e) Una vez concretadas las instancias anteriores, y concretada la firma del convenio urbanístico concertado entre las partes (Emprendedor-Departamento Ejecutivo Municipal), se remitirá el mismo al Concejo Deliberante de la Ciudad de Plottier para su análisis, solicitando su aprobación mediante la Ordenanza Municipal pertinente.
f) El seguimiento de la implementación del convenio urbanístico estará a cargo de la autoridad de aplicación del presente código de planeamiento urbano rural.
g) La aprobación del convenio urbanístico, dará lugar a la modificación del Código de Planeamiento Urbano Rural vigente, únicamente en e la superficie territorial afectada al convenio, según los contenidos acordados y aprobados en el mismo.
h) En caso de no cumplir con los compromisos acordados, la autoridad de aplicación fijará multas o adicionales aportes en forma de terrenos.

16. BANCO MUNICIPAL DE TIERRAS

Se creará el Banco Municipal de Tierras, a efectos de administrar las tierras de dominio municipal existente, así como aquellas que se incorporen al patrimonio municipal, a partir del desarrollo de nuevos emprendimientos urbanísticos, el cumplimiento de convenios urbanísticos u otros medios de adquisición. Las tierras que integren el Banco Municipal de Tierras, serán administradas por la autoridad de Aplicación del Código de Planeamiento Urbano Rural vigente y tendrán como fin único la construcción y desarrollo de equipamiento e infraestructura pública para el mayor beneficio de la comunidad de Plottier.

17. FONDO PARA EL DESARROLLO URBANO RURAL (FODUR)

Se creará el Fondo para el Desarrollo Urbano Rural de la ciudad de Plottier, a efectos de administrar los bienes financieros resultantes del cumplimiento de convenios urbanísticos.
Los fondos que se incorporen al FODUR, tendrán el único y exclusivo fin de concretar obras de equipamiento y/o infraestructura de uso público, destinadas a resolver deficiencias o realizar mejoras que favorezcan el desarrollo de los espacios urbanos o rurales del ejido municipal. Este fondo será administrado por la autoridad de Aplicación del Código de Planeamiento Urbano Rural vigente teniendo en cuenta el mayor beneficio para la comunidad de Plottier.

18. RESTRICCIONES DE USO DE SUELO EN ZONAS RIBEREÑAS

A efectos de la regulación de los usos de suelo en zonas ribereñas, se aplicarán las siguientes disposiciones:

18.1. Todo uso de suelo que se pretenda desarrollar en zonas ribereñas tendra que ceder al dominio publico, un camino que dara continuidad al paseo costanero. La franja cedida tendra un ancho minimo de 25 mts y sera paralela a la linea de inundacion, con una cota de nivel superior a ella, con una distancia desde el eje de calle a la L.I. no mayor a 50 mts.

ANEXO I

ARBOLADO URBANO

ARBOLADO URBANO DE LA CIUDAD DE PLOTTIER

DIRECTRICES GENERALES

1) Implementar un arbolado urbano sostenible, eligiendo especies vegetales adaptadas al medio, con consumo racional del agua, minimizando y reciclando residuos vegetales.

2) Mantener una relación de mutua armonía entre el arbolado y el entorno construido.

3) Contar con un conjunto de diez especies como mínimo, para que en las futuras plantaciones exista la variedad requerida, lo que significa una medida sustentable. Mezclar especies indica un mantenimiento oneroso desde el punto de vista de la poda y de las condiciones sanitarias. Debe existir una única especie por calle, barrio o sector permite que el árbol actúe como elemento integrador que unifica, permite que se forme un túnel de sombra en verano y un mantenimiento diferenciado y adecuado por especie.

4) La distancia de plantación, se fijará en función del desarrollo de la especie a plantar.

5) El arbolado de alineación en veredas tiene las siguientes funciones:

- Proveer sombra, absorber ruidos, oxigenar el ambiente, cobijar a las aves, aumentar la humedad relativa del aire, reducir la temperatura ambiente, la polución ambiental, la acción de los vientos y la erosión.

- Mejorar el aspecto estético de la ciudad: las distintas especies caracterizan a un barrio o a la ciudad.

- Encausa el movimiento de la gente hacia un determinado lugar ya que una calle bien arbolada invita a la gente a introducirse en ella.

- Actúa como elemento de contraste con lo construido en las parcelas y con los elementos de infraestructura existentes en las veredas.

- Unifica y ordena un espacio que por diversidad de estilos y escalas aparece como arquitectónicamente caótico ya que la repetición de formas genera la unidad.

- Forma barreras contra vistas indeseables.

- Aporta formas libres y movimiento.

- Nos acerca a la naturaleza con sus colores y perfumes.

- Actuar sobre el comportamiento humano.

DIRECTRICES PARTICULARES

TIPO DE ESPACIO PÚBLICO

Itinerarios Urbanos

En los itinerarios donde dominen sectores destinados a calle pública, éstas tendrán arbolado de alineación. En itinerarios de grandes superficies tendrán un desarrollo particular del proyecto de dicho espacio.

Veredas

Se adopta como criterio la relación de espacio - especie a plantar. Se considera que el ancho de vereda es el que deberá tenerse en cuenta a la hora de la elección de la especie a plantar, puesto que el desarrollo de su copa deberá convivir lo más convenientemente posible en el espacio urbano en el que se implante.

IMPLANTACIÓN DEL ARBOLADO

Características Morfológicas de los Árboles

La forma externa que un árbol adopta, queda definida por los siguientes aspectos:

1) Porte: Se denomina así al diámetro transversal de la copa del árbol en la etapa de mayor desarrollo. Las diversidades de porte pueden condensarse en tres categorías:
   - Pequeño porte: diámetros de copa menores a los 2.50 metros.
   - Mediano porte: diámetros entre 2.50 y 5.00 metros
   - Alto porte: diámetros mayores a los 5.00 metros.
2) Tamaño del sistema radicular del árbol: Es proporcional y casi equivalente al porte, por tanto a mayor porte mayor raíz. El tamaño de la raíz y la copa del árbol determinan la distancia de plantación.
3) Follaje: El follaje presenta tres cualidades de suma importancia en el momento de elegir una especie para implantar en el entorno urbano.
   - Densidad: La densidad del follaje influye en la visibilidad, el paso de la luz solar, los vientos, los ruidos, los olores, la lluvia, y la contaminación.
   - Forma: A los fines prácticos se agrupan a los árboles según su forma de copa en seis tipos: forma de palma, esférico, ovalado horizontal, cónico, globular, ovalado vertical.

- Permanencia: Existen especies de árboles que pierden la totalidad o parte de sus hojas, a diversos intervalos de tiempo, su follaje no es permanente y será el que se adopte para todos los casos en que se esté hablando de árbol de vereda, árbol de "hoja caduca".

Características elegibles en una especie de árbol de alineación (paralelo a la línea municipal)

1) Forma y tamaño adecuado al espacio en que se va a desarrollar.

2) Fuste libre de ramas de aproximadamente 3m a 3,5m (en calles comerciales) y de 2,2m en calles angostas.

3) Hojas caducas con caída temprana y no prolongada.

4) Desarrollo relativamente rápido.

5) Resistente a plagas y enfermedades.

6) Resistente a la acción del viento.

7) Resistente a la polución, tener frutos que no manchen y buena inserción de las ramas para evitar accidentes a los usuarios a causa de la debilidad o fragilidad de la madera.

8) Con sistema radicular profundo y no excesivamente vigoroso.

9) Una especie no deberá comprometer más del 10% del arbolado público total. No se plantará más de un 20 % de especies de un mismo género. No se plantará más de un 30 % de especies de una familia.

10) Las especies elegidas deben ser variadas para evitar riesgos de desastres ecológicos ante la aparición de plagas o enfermedades que las afecten.

LISTADO DE ESPECIES A UTILIZAR SEGÚN TIPO DE VEREDA

ANCHO DE VEREDA MENOR A 2.50 METROS

ESPECIE Denominación Botánica	Denominación Corriente	Menor a 2.50 m. Franja de Césped Cazuelas de 0.80 x 0.80
Lagerstroemia indica	Crespón	Dist. de Plant. >4 y <5 m.
Fraxinus excelsior aurea	Fresno Dorado	Dist. de Plant. >4 y <5 m.

Ejemplo: Crespón (*Lagerstroemia indica)*



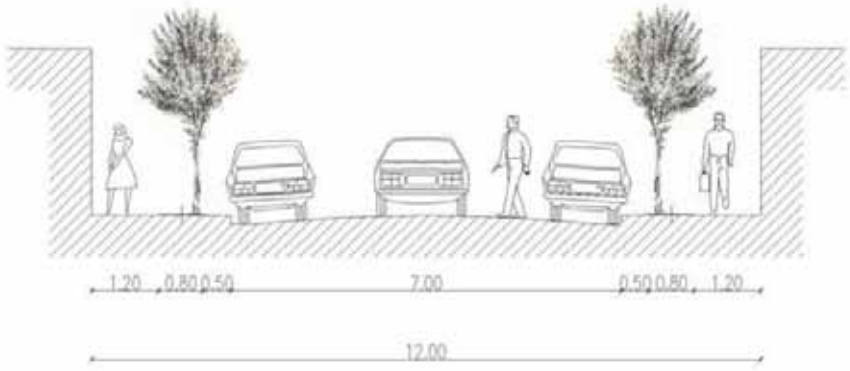

ANCHO DE VEREDA de 2.50 a 3.00 metros (con retiro de Línea Municipal)

ESPECIE Denominación Botánica	Denominación Corriente	2.50 – 3.00 m. con Retiro de Línea Municipal Franja de Césped Cazuelas de 0.90 x 0.90
Lagerstroemai ilndica	Crespón	Dist. de Plant. >4 y <5 m.
Fraxinus excelsior aurea	Fresno Dorado	Dist. de Plant. >4 y <5 m.
Cersis siliquastrum	Árbol de Judea	Dist. de Plant. >4 y <5 m.

Ejemplo: Fresno Dorado *(Fraxinus excelsior aurea)*

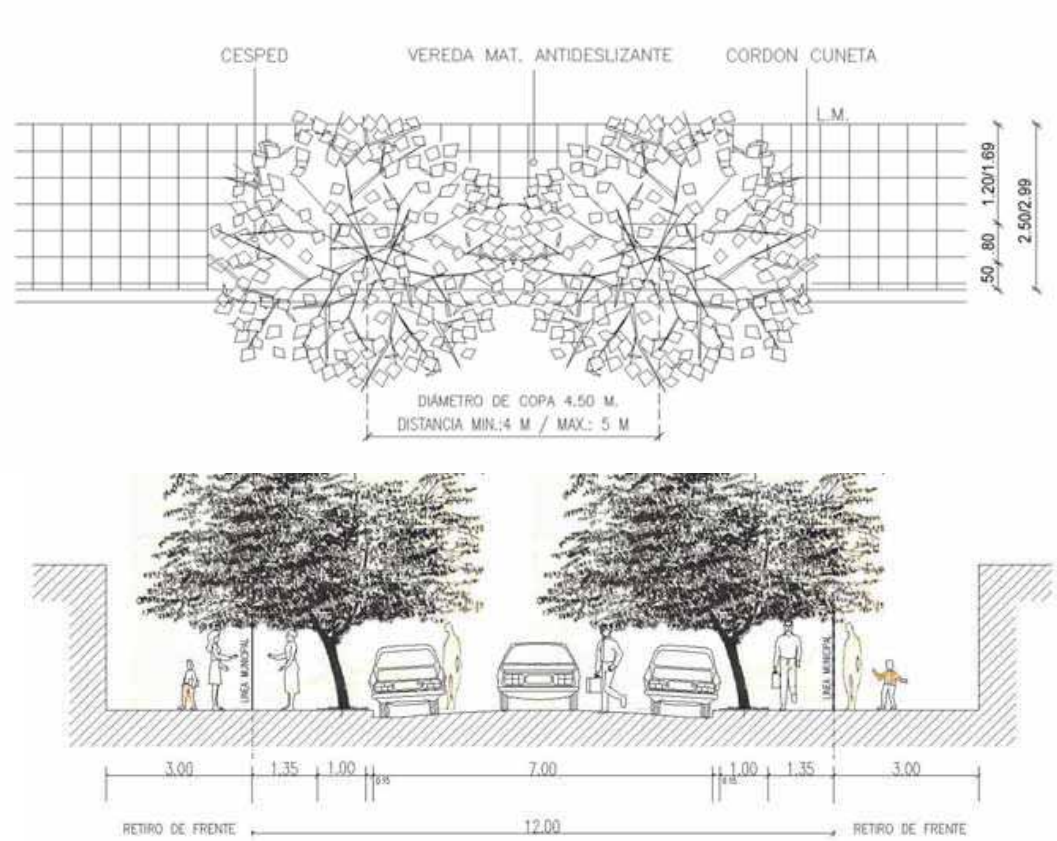

NCHO DE VEREDA 2.50 A 3.00 metros sin retiro de Línea Municipal

ESPECIE Denominación Botánica	Denominación Corriente	2.50 – 3.00 m. sin Retiro de Línea Municipal Franja de Césped Cazuelas de 0.90 x 0.90
Lagerstroemia indica	Crespón	Dist. de Plant. >4 y <5 m.
Fraxinus excelsior aurea	Fresno Dorado	Dist. de Plant. >4 y <5 m.
Cersis siliquastrum	Árbol de Judea	Dist. de Plant. >4 y <5 m.
Prunus cerasifera	Ciruelo de Jardín	Dist. de Plant. >4 y <5 m.

Ejemplo: Ciruelo de Jardín *Prunus cerasifera*

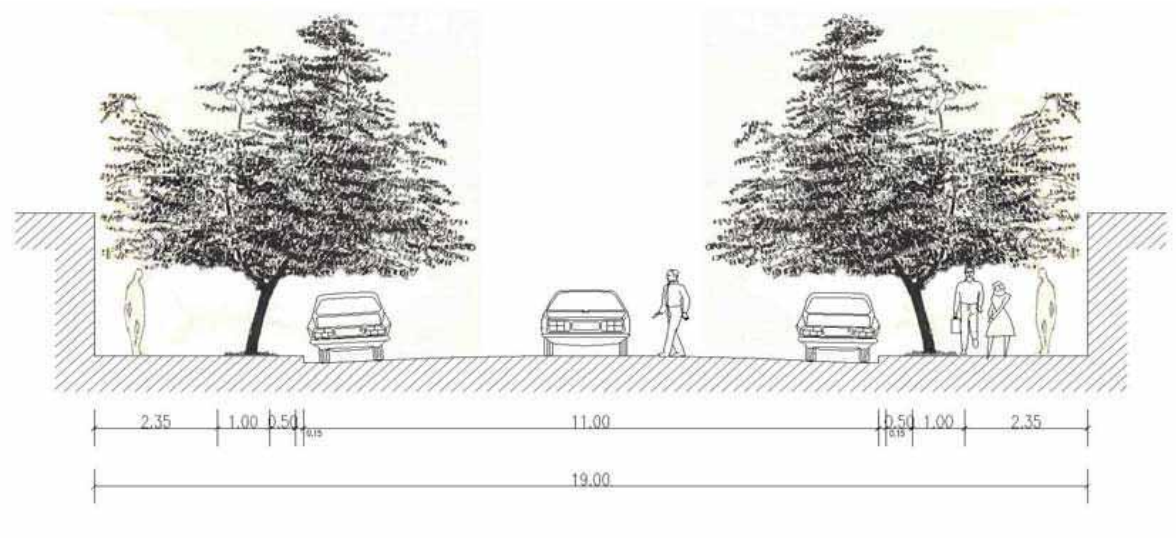

ANCHO DE VEREDA 3.00 A 4.00 metros sin retiro de Línea Municipal

ESPECIE Denominación Botánica	Denominación Corriente	3.00 – 4.00 m. sin Retiro de Línea Municipal Franja de Césped Cazuelas de 0.90 x 0.90
Acacia visco	Acacia Visco	Dist. de Plant. >4 y <5 m.
Betula pendula	Abedul	Dist. de Plant. >4 y <5 m.
Cersis siliquastrum	Arbol de Judea	Dist. de Plant. >4 y <5 m.
Prunus cerasifera	Ciruelo de Jardin	Dist. de Plant.>4 y <5 m.
Catalpa bignonioides	Catalpa	Dist. de Plant.>4 y <5 m.
Eleagnus angustifolia	Olivillo	Dist. de Plant.>4 y <5 m.
Fraxinus excelsior	Fresno Europeo	Dist. de Plant.>4 y <5 m.

Ejemplo: Arbol de Judea *Cersis siliquastrum*

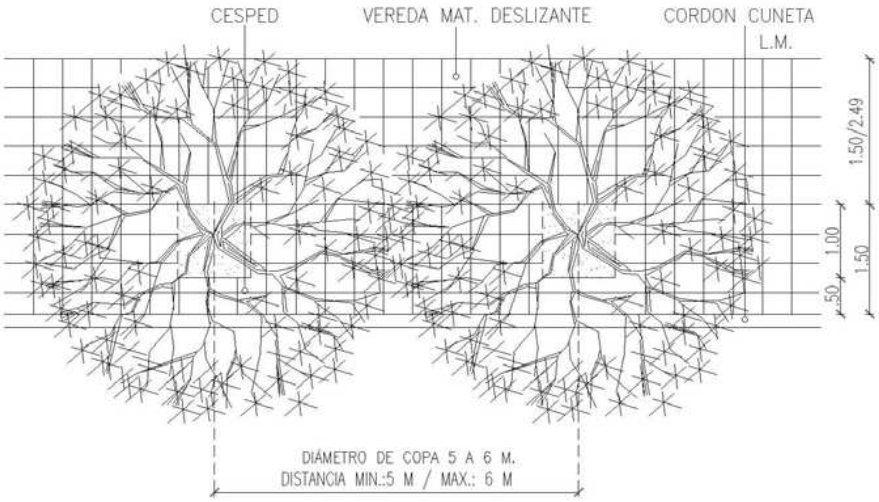

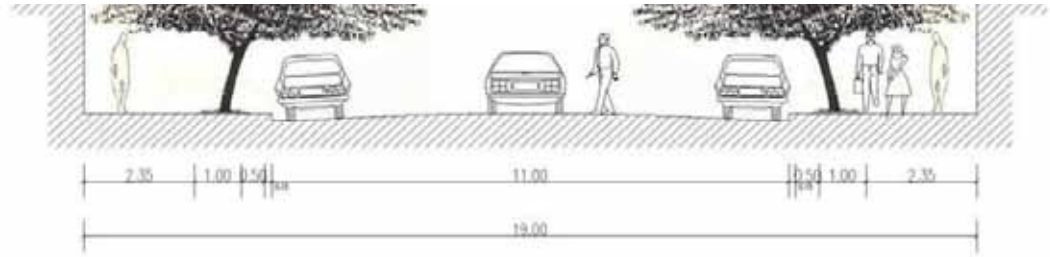

ANCHO DE VEREDA 3.00 A 4.00 metros con retiro de Línea Municipal

ESPECIE Denominación Botánica	Denominación Corriente	3.00 – 4.00 m. con Retiro de Línea Municipal Franja de Césped Cazuelas de 0.90 x 0.90
Acacia visco	Acacia Visco	Dist. de Plant. >5 y <6 m.
Betula pendula	Abedul	Dist. de Plant. >5 y <6 m.
Acer negundo	Arce común	Dist. de Plant. >5 y <6 m.
Acer negundo	Arce común (Variegado)	Dist. de Plant. >5 y <6 m.
Catalpa bignonioides	Catalpa	Dist. de Plant.>5 y <6 m.
Aesculus carnea	Castaño de Indias	Dist. de Plant. >5 y <6 m.
Fraxinus excelsior	Fresno Europeo	Dist. de Plant. >5 y <6 m.
Albizzia julibrissin	Acacia de Constantinopla	Dist. de Plant. >5 y <6 m.
Alnus glutinosa	Aliso	Dist. de Plant.>5 y <6 m.
Fraxinus americana	Fresno Americano	Dist. de Plant. >5 y <6 m.
Gleditsia tricanthos I.	Acacia Negra sin espinas	Dist. de Plant. >5 y <6 m.
Gleditsia tricanthos I. S.	Acacia Negra Dorada	Dist. de Plant. >5 y <6 m.
Liquidambar styraciflua	Liquidambar	Dist. de Plant. >5 y <6 m.
Liriodendron tulipifera	Tulipanero	Dist. de Plant. >5 y <6 m.
Melia azedarach	Paraíso Común	Dist. de Plant. >5 y <6 m.
Melia azedarach umbrac	Paraíso Sombrilla	Dist. de Plant. >5 y <6 m.
Morus alba	Morera Híbrida	Dist. de Plant. >5 y <6 m.
Robignia Hispida.	Acacia rosada	Dist. de Plant. >5 y <6 m.
Robinia pseudoacacia A	Acacia blanca	Dist. de Plant. >5 y <6 m.
Sophora japonica	Sofora	Dist. de Plant.>5 y <6 m.
Tilia cordata	Tilo	Dist. de Plant.>5 y <6 m.

Ejemplo: Tilo *(Tilia cordata)*

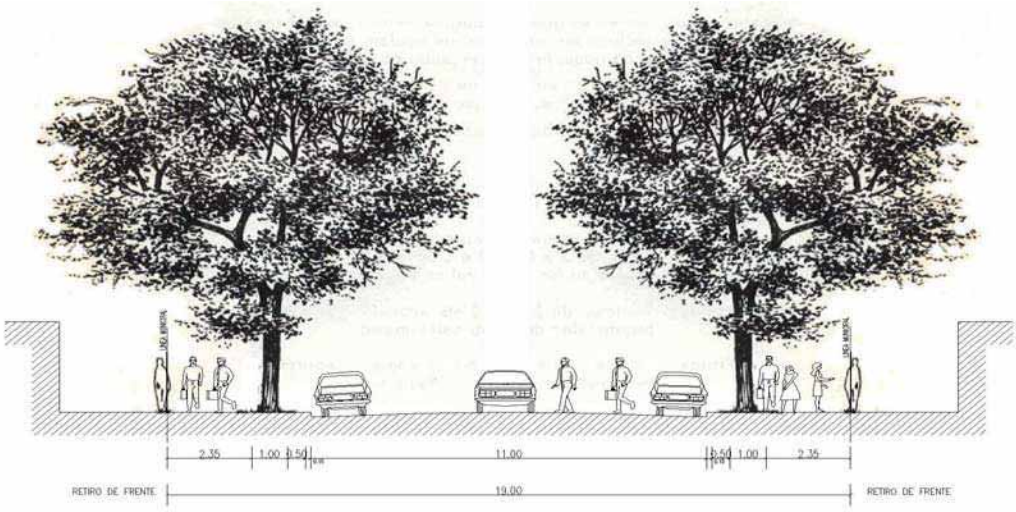

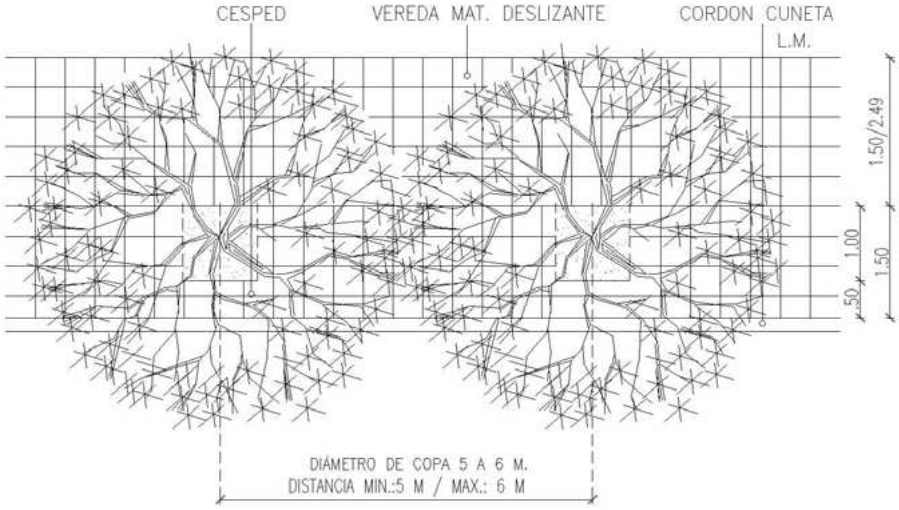

ANCHOS DE VEREDA MAYOR A LOS 4.00 METROS

ESPECIE Denominación Botánica	Denominación Corriente	Mayor 4.00 m. Franja de Césped Cazuelas de 0.90 x 0.90
Aesculus hipocastaneum	Castaño de Indias	Dist. de Plant. >5 y <6 m.
Betula pendula	Abedul	Dist. de Plant. >5 y <6 m.
Acer negundo	Arce común	Dist. de Plant. >5 y <6 m.
Acer negundo	Acer Variegado	Dist. de Plant.>5 y <6 m.
Catalpa bignonioides	Catalpa	Dist. de Plant.>5 y <6 m.
Fraxinus excelsior	Fresno Europeo	Dist. de Plant.>5 y <6 m.
Alnus glutinosa	Aliso	Dist. de Plant.>5 y <6 m.
Fraxinus americana	Fresno Americano	Dist. de Plant.>5 y <6 m.
Gleditsia tricanthos I.	Acacia Negra sin espinas	Dist. de Plant.>5 y <6 m.
Gleditsia tricanthos I. S.	Acacia Negra Dorada	Dist. de Plant.>5 y <6 m.
Gleditsia tricanthos. I.R.L.		Dist. de Plant.>5 y <6 m.
Liquidambar styraciflua	Liquidambar	Dist. de Plant.>5 y <6 m.
Liriodendron tulipifera	Tulipanero	Dist. de Plant.>5 y <6 m.
Melia azedarach umbrac	Paraíso Sombrilla	Dist. de Plant.>5 y <6 m.
Morus alba	Morera Híbrida	Dist. de Plant.>5 y <6 m.
Robinia pseudoacacia C.	Acacia blanca	Dist. de Plant.>5 y <6 m.
Acer pseudoplatanus	Arce canadiense	Dist. de Plant > 6 m.
Platanus acerifolia	Platano	Dist. de Plant > 6 m.
Sophora japonica	Sofora	Dist. de Plant.>5 y <6 m.
Tilia cordata	Tilo	Dist. de Plant.>5 y <6 m.

Ejemplo: Plátano *(Platanus acerifolia)*

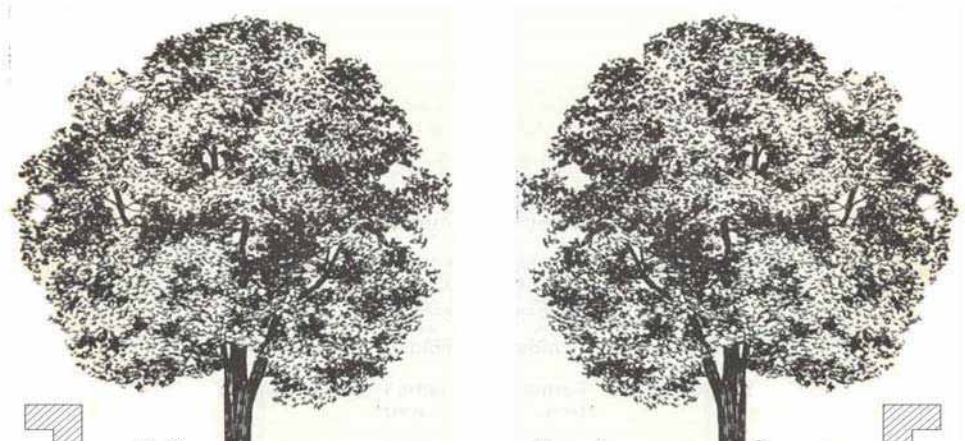

ESPECIES PARA AREAS COMERCIALES.

De acuerdo a las características del fuste y del follaje, la especie elegida deberá cumplir con el ancho de vereda correspondiente. Tener en cuentaque en zona comercial las cazuelas deben ser de 0.90x0.90mts.

Ejemplo: Ciruelo de Jardín *(Prunus cerasifera)*

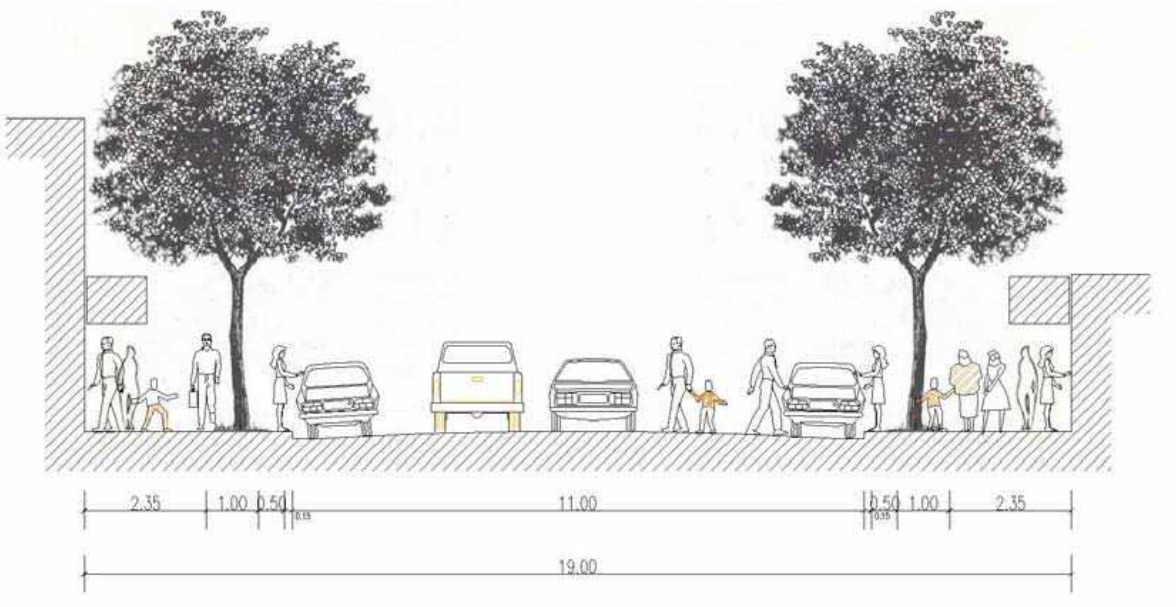

DEL ARBOL Y LAS EDIFICACIONES.

1) Todo proyecto de construcción, reforma edilicia o actividad urbana en general, deberá respetar el arbolado público existente, o el lugar reservado para futuras plantaciones.

2) La Municipalidad no aprobará presentaciones de planos de edificación, refacción o modificación de construcciones, cuyos accesos vehiculares o cocheras, sean proyectadas frente a árboles existentes en el frente, no siendo causal de su erradicación, ni el proyecto, ni los requerimientos de la obra.

3) A fin de obtener la Licencia Comercial, el interesado deberá presentar plano de vereda con indicación de las especies existentes o a plantar junto a la documentación exigida por la Dirección de Obras Particulares, dependiente de la Subsecretaría de Obras, Planeamiento y Catastro de la Municipalidad de Plottier. La plantación será verificada por la Dirección de Espacios Verdes.

ERRADICACION DE ÁRBOLES.

1) Árbol que se pretende erradicar: cada árbol existente posee un valor estético, ambiental, físico, histórico y cultural que se deberá evaluar a través de la Dirección de Espacios Verdes. La erradicación del mismo será estipulada de acuerdo a un valor monetario, especificado en la normativa vigente mediante módulos.

2) En casos excepcionales y cuando la disposición de los árboles fuese tal que su extracción se hiciera imprescindible, el Departamento Ejecutivo (previo informe que al respecto emita la Dirección de Espacios Verdes) decidirá en definitiva. Los gastos que demanden la erradicación de la especie forestal, correrán por cuenta del propietario.

OBLIGACION EN LA PLANTACIÓN Y EL MANTENIMIENTO

1) El frentista, ya sea locatario, o locador del inmueble que ocupa tiene la obligación de la plantación y mantenimiento de las especies abóreas que deben ir ubicadas sobre vereda.

2) La plantación de arbolado de alineación debe responder a una planificación previa a fin de asegurar el óptimo desarrollo de las especies elegidas para que sea posible su mantenimiento.

3) Cuando hay especies implantadas, deben considerarse las distancias del árbol a implantar con respecto a los ejemplares existentes.

4) La plantación deberá estar autorizada por el municipio.

5) Con respecto a la distancia de las esquinas, elprimer árbol no podrá ser plantado dentro del área correspondiente entre la prolongación de ochava, a un lado y al otro y las líneas de plantación respectivas.

SISTEMAS DE RIEGO

1) Se recomienda el sistema de riego por goteo para un mejor aprovechamiento del recurso agua y la conservación de las distintas especies del arbolado

2) Es obligación de cada frentista, al construir o refaccionar las veredas, dejar el lugar para forestar, y construir las cazuelas en los casos de que la vereda de material llegue hasta el cordón cuneta, o dejar el espacio para forestar.

ARBOLADO Y ESTACIONAMIENTO VEHICULAR.

Deberá existir una distancia mínima de 0,50m entre el borde de lalínea oficial de vereda y la cazuela, a fin de facilitar el acceso al vehículo estacionado evitando daños sobre el árbol, al abrir las puertas del mismo.

RELACION DEL ARBOLADO CON LA INFRAESTRUCTURA.

1) El árbol de vereda necesita un espacio aéreo y otro subterráneo.

2) En lo que respecta al espacio aéreo, los postesde alumbrado y conducción de la energía deberán estar ubicados a la mitad de la distancia de plantación de árboles, para que los mismos se puedan desarrollar adecuadamente sin interferir con el servicio.

3) En trabajos que afecten la supervivencia del árbol, como es el zanjeado cercano a la línea de plantación, se requerirá la presentación de un proyecto de instalación de redes por parte del organismo responsable de su instalación, el cual deberá ser aprobado por la Subsecretaría de Obras, Planeamiento y Catastro en conjunto con la Dirección de Espacios Verdes.

RELACION DEL ARBOLADO CON LOS CARTELES COMERCIALES Y MARQUESINAS

En aquellas veredas que se admita la instalación de carteles comerciales y/o marquesinas, éstos deberán ajustar su ubicación a la de los árboles existentes y no deberán afectar la estructura arbórea. Si el árbol va a ser plantado, debe alejarse lo suficiente del cartel existente como para que se pueda formar adecuadamente.

TAMAÑO DEL ARBOL AL MOMENTO DE LA PLANTACION Y VANDALISMO.

1) El árbol elegido para la plantación deberá tener un fuste mínimo relacionado con un diámetro mínimo de tronco de 3.5 cm, los cualesserán definidos de acuerdo al uso de la vereda: residencial, comercial.

2) Un árbol de escaso desarrollo, al alcance de lamano, es susceptible de mayores ataques y roturas y los porcentajes de fracaso en la plantación se hacen considerablemente mayores.

DIMENSIONES DE CAZUELAS

De acuerdo a los anchos de vereda, se deberá dejar una cazuela de 0.90 x 0.90m. En el caso en que se dispongan franjas verdes el ancho puede reducirse a 0,80m.

En veredas menores o iguales a 2.50 m la cazuela será de 0. 80 x 0.80 m.

CRITERIOS DE MANEJO TECNICO AMBIENTALES

1) A fin de lograr la biodiversidad y evitar la aparición de plagas se generarán franjas o bloques de uniformidad que se distribuirán en la ciudad para obtener heterogeneidad biológica y espacial.
2) En función de los ciclos de cultivo para cada especie y de la superficie destinada a la producción, se planificará el vivero municipal. De acuerdo a las metas en el tiempo, y a la producción de árboles, se promoverá a los viveros privados para la siembra de las especies requeridas.
3) Se deberá capacitar al personal tanto operativo, como técnico del municipio a fin de encontrar soluciones a los problemas que el arbolado pudiera presentar.
4) Se establecerán normas y estándares de trabajo para llevar a cabo las tareas, y determinar la calidad de los servicios: tipo y calidad de árboles, y plantación. Mantenimiento: poda, fertilización, y tratamientos sanitarios. Minimización y reciclado de residuos vegetales. Seguridad del Trabajo. Valorización de los árboles.

CAPITULO II

PROCEDIMIENTOS DE FACTIBILIDAD TERRITORIAL AMBIENTAL (FTA)

1. INTRODUCCION

Los procedimientos que se presentan a continuación, se elaboraron en base a los postulados de la Carta Orgánica de la Ciudad de Plottier, los parámetros normativos expresados en el presente documento de actualización del Código de Planeamiento Urbano Rural vigente (Ord. 2.315/04), enunciados específicos de la Ley Provincial de Medio Ambiente (Ley 1.875) y su decreto reglamentario (2.656/99), a los cuales adhiere la Municipalidad de Plottier por medio de la Ordenanza 1.899/00 y la Ordenanza 1.913/00, relativa al procedimiento de subdivisión y fraccionamiento urbano.
Todos los trámites previstos en el presente capítulo, se iniciarán con la llegada del expediente de "solicitud de factibilidad" a la Subsecretaría de Obras Planeamiento y Catastro.

2. ALCANCES:

Toda actividad económica, proyecto urbanístico, de equipamiento o infraestructura, así como toda obra nueva a ejecutar que pretenda desarrollarse dentro del ejido municipal de Plottier, deberá contar para su aprobación con un dictamen de factibilidad territorial ambiental (FTA) expedido por la Municipalidad de Plottier, a efectos de garantizar que tanto sus etapas constructivas como de funcionamiento, se concreten respetando la calidad ambiental de la ciudad y su entorno, así como el desarrollo saludable y armónico de los espacios urbanos y rurales.

3. FINALIDADES:

El procedimiento FTA tiene como finalidades:

a. Determinar si el proyecto o actividad propuesta, resulta compatible con los usos de suelo previstos para la zona en la que se pretende localizar.

b. En caso de resultar compatible (viabilidad de uso de suelo), fijar las condiciones y requisitos de índole proyectual y ambiental que deberán cumplimentarse por parte del proponente, a efectos tanto de la prosecución del trámite, como de la posterior vigencia de la factibilidad territorial ambiental otorgada, una vez iniciada la actividad propuesta.

4. APLICACIÓN:

El procedimiento FTA se implementará de acuerdo a la complejidad de la actividad o proyecto bajo análisis, previéndose diversas instancias acordes a la clasificación subsiguiente y las distintas categorías de evaluación previstas.

Las actividades sujetas a FTA, han sido clasificadas en:

- Proyectos Urbanísticos
- Actividades Económicas
- Obras Nuevas

Dentro de esta clasificación básica se establecieron las distintas categorías de análisis y evaluación, acordes al grado presunto de incidencia en el ordenamiento territorial y el impacto ambiental potencial.
Para cada categoría se definieron distintos tipos de trámite, los cuales se visualizan en los tres cursogramas de factibilidad previstos.

5. UNIDAD TÉCNICA:

En caso de que la complejidad del proyecto en trámite lo amerite, se dispondrá la convocatoria y conformación de la Unidad Técnica a efectos de evaluar su factibilidad. Esta unidad estará constituida por profesionales y referentes de las áreas municipales que tengan injerencia en su evaluación, siendo la Subsecretaria de Obras Planeamiento y Catastro o el área que en el futuro la reemplace, el organismo encargado de su conformación y coordinación.
Una vez producido, el dictamen de la Unidad Técnica será elevado el ejecutivo municipal para la toma de decisión, debiendo constar en el mismo la argumentación técnica que lo sustenta.
La Unidad Técnica se creará por medio de un decreto emanado del ejecutivo municipal, y su reglamentación se realizará por medio de una resolución de la Subsecretaría de Obras Planeamiento y Catastro.

6. ESTUDIOS AMBIENTALES

En los trámites relativos a la factibilidad de actividades económicas y obras nuevas, se utilizarán los procedimientos y términos de referencia vigentes en la Ord. 1.899/00 (Dec. Pcial. N° 2.656/99).
En los trámites relativos a la factibilidad de proyectos urbanísticos, si bien se aplicarán los procedimientos previstos en la mencionada norma, se utilizarán los términos de referencia que se encuentran en el Anexo I del presente capítulo, los cuales fueron diseñados específicamente para la evaluación de este tipo de proyectos.
De acuerdo a la complejidad del proyecto urbanístico a evaluar, la autoridad municipal determinará la solicitud de:

- IIUA (Informe de Impacto Urbano Ambiental)
- EIUA (Estudio de Impacto Urbano Ambiental)

7. RESPONSABLE AMBIENTAL

En aquellos casos de proyectos urbanísticos, obras o actividades económicas a desarrollar u objeto de auditoria, cuya complejidad y/o incidencia ambiental lo ameriten, el municipio podrá requerir al titular del emprendimiento la designación de un "responsable ambiental", quien tendrá a su cargo la aplicación efectiva de las medidas de prevención y mitigación de impactos ambientales previstas en el Plan de Gestión Ambiental.

El responsable ambiental deberá ser presentado formalmente ante el municipio por el titular del emprendimiento, por medio de una nota de presentación que acredite su identidad y vinculación con la empresa, en la instancia de aplicación del procedimiento FTA, ante el requerimiento de la autoridad municipal.

El municipio podrá determinar que el responsable ambiental a designar, sea un profesional de especialidad ambiental matriculado y registrado en el "Registro Provincial de Prestadores de Servicios Ambientales – REPPSA" o el registro que en el futuro lo reemplace.

El responsable ambiental, deberá acreditar y/o certificar el cumplimiento de las medidas previstas en el Plan de Gestión Ambiental y presentar documentación respaldatoria, a efectos de la fiscalización ambiental de la actividad, por parte de la autoridad municipal de control.

CURSOGRAMA FTA – TRÁMITES DE PROYECTOS URBANÍSTICOS

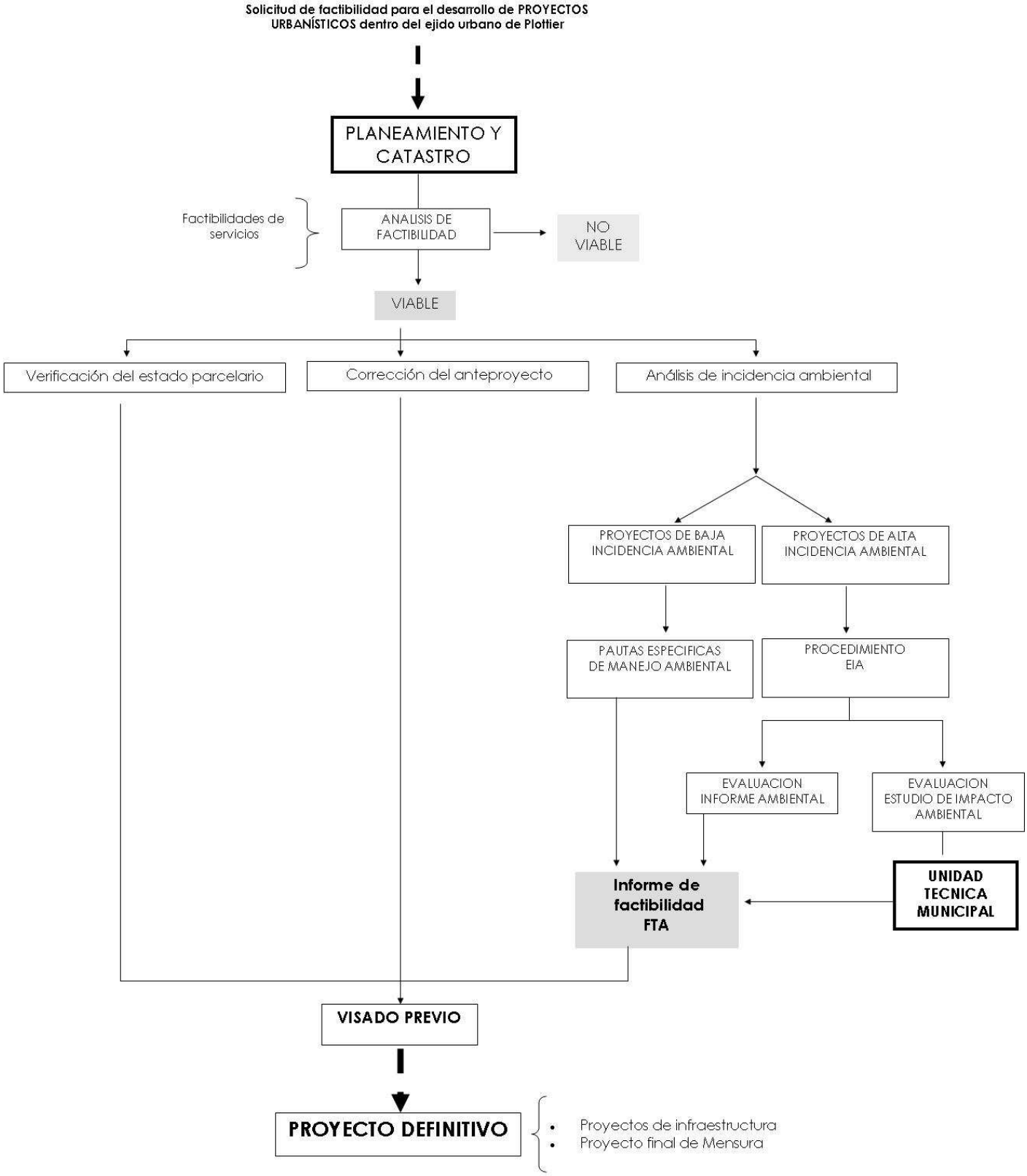

CURSOGRAMA FTA – TRÁMITES DE HABILITACIÓN DE ACTIVIDADES ECONÓMICAS

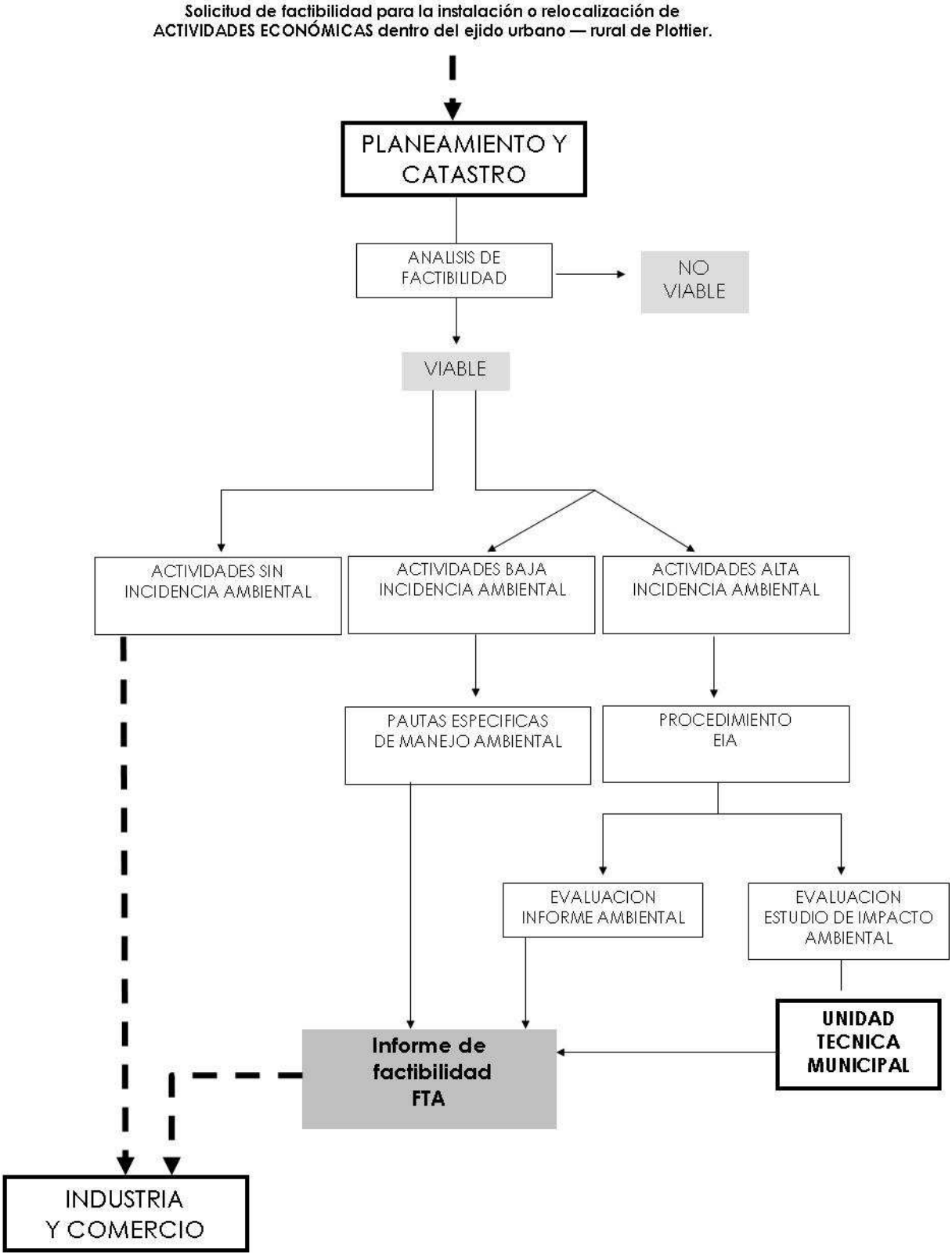

CURSOGRAMA FTA – TRÁMITES DE OBRAS NUEVAS

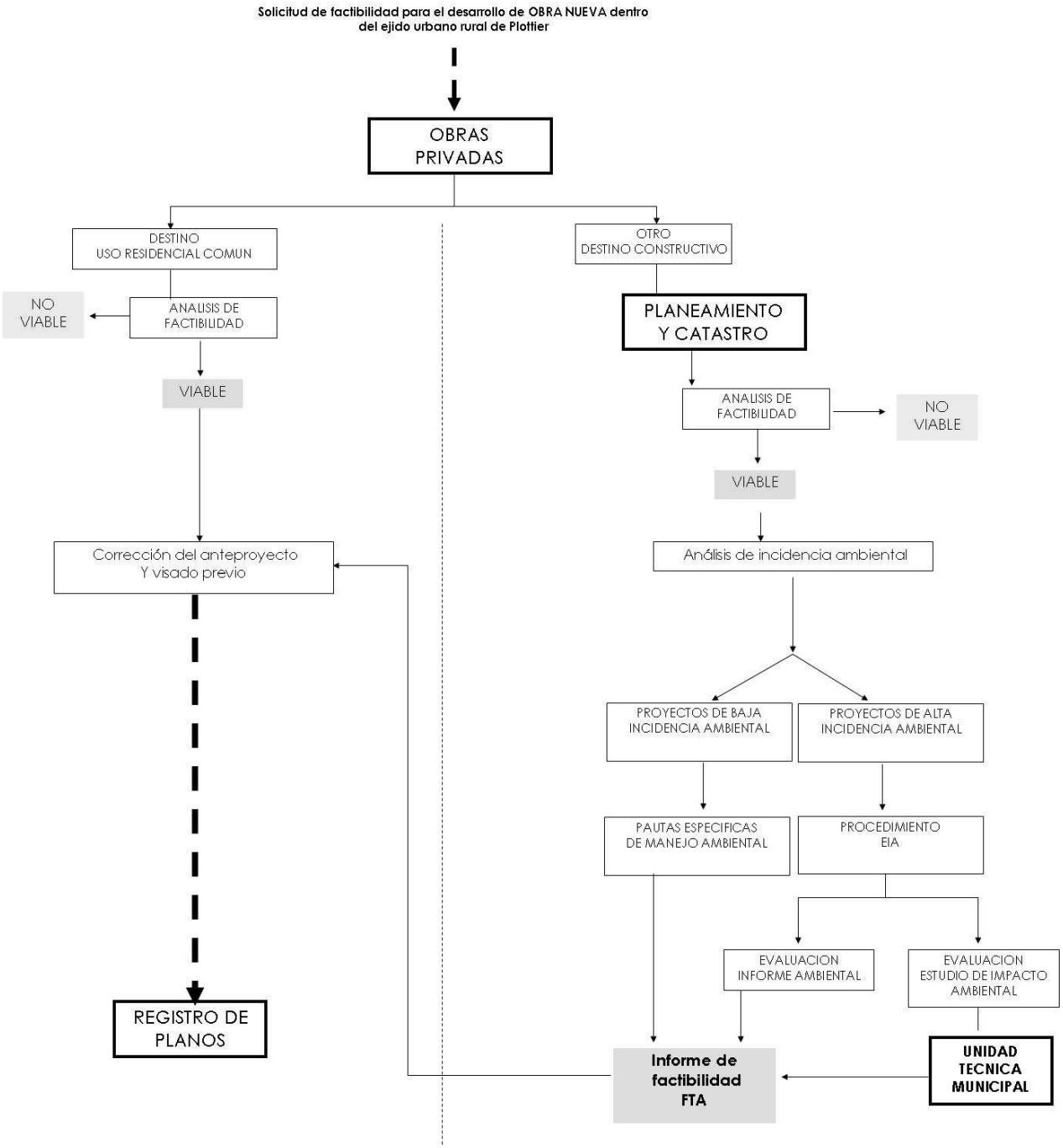

ANEXO I
TÉRMINOS DE REFERENCIA

TÉRMINOS DE REFERENCIA PARA LA ELABORACIÓN DE INFORMES DE IMPACTO URBANO AMBIENTAL – IIUA.

I. DATOS GENERALES
1 RAZÓNSOCIAL
2 DOMICILIO LEGAL
3 DOMICILIO ESPECIAL PARA NOTIFICACIONES
4 TELÉFONO
5 E-MAIL
6 ACTIVIDAD PRINCIPAL:
7 RESPONSABLE DE LA AUDITORIA AMBIENTAL
8 EQUIPOTÉCNICO
II. RESUMEN EJECUTIVO
III. UBICACIÓN Y DESCRIPCIÓN DEL PROYECTO
1 PLANO DEL PROYECTO
2 NOMBRE DEL PROYECTO
3 OBJETIVOS Y JUSTIFICACIÓN
4 LOCALIZACIÓN FÍSICA
5 DESCRIPCIÓN DEL PROYECTO Etapas y Acciones Del Proyecto. Movimientos de Suelo Previstos
8 DESCRIPCIÓN DEL ENTORNO INMEDIATO
9 DETERMINACION DEL AREA DE AFECTACION DIRECTA E INDIRECTA
IV. DESCRIPCION Y ANALISIS DEL MEDIO NATURAL Y SOCIOECONOMICO
1 MEDIO INERTE. Planialtimetría. Características geotécnicas y geomorfologías del suelo. Hidrología superficial y subterránea
2 MEDIO BIOTICO
3 MEDIO PERCEPTUAL
4 MEDIO SOCIOECONOMICO
V. ASPECTOS URBANISTICOS
1. DIRECTRICES URBANISTICAS DE LA ZONA Indicadores. Usos de Suelo. Sistema de movilidad urbana
2. EQUIPAMIENTO EXISTENTE Equipamiento Social. Salud. Educación. Seguridad. Administración.
Comercios y Servicios
3. COBERTURA DE SERVICIOS E INFRAESTRUCTURA Energía eléctrica. Gas natural. Cloacas. Agua
Potable. Asfalto. Desagües. Comunicaciones
V. EVALUACIÓN DE LOS IMPACTOS Y EFECTOS AMBIENTALES
1 ACCIONES QUE PRODUCEN IMPACTO AMBIENTAL
2 FACTORES AMBIENTALES AFECTADOS
3 MATRIZ DE IMPACTOS AMBIENTALES
4 VALORACION DE IMPACTOS AMBIENTALES
VI. PLAN DE GESTION AMBIENTAL
1 PLAN DE GESTION AMBIENTAL DE LA ETAPA CONSTRUCTIVA
2 PLAN DE GESTION AMBIENTAL DE LA ETAPA DE FUNCIONAMIENTO
3 CRONOGRAMAS DE CUMPLIMIENTODE ACCIONES
VII. REFERENCIAS
1 BIBLIOGRAFIA CONSULTADA
2 NORMATIVA APLICABLE NACIONAL, PROVINCIAL, MUNICIPAL.

TÉRMINOS DE REFERENCIA PARA LA ELABORACIÓN DE ESTUDIOS DE IMPACTO URBANO AMBIENTAL – EIUA.

I. DATOS GENERALES
1 RAZÓNSOCIAL
2 DOMICILIO LEGAL
3 DOMICILIO ESPECIAL PARA NOTIFICACIONES
4 TELÉFONO
5 E-MAIL
6 ACTIVIDAD PRINCIPAL:
7 RESPONSABLE DE LA AUDITORIA AMBIENTAL
8 EQUIPOTÉCNICO
II. RESUMEN EJECUTIVO
III. UBICACIÓN Y DESCRIPCIÓN DEL PROYECTO
1 PLANO DEL PROYECTO
2 NOMBRE DEL PROYECTO
3 OBJETIVOS Y JUSTIFICACIÓN
4 LOCALIZACIÓN FÍSICA
5 DESCRIPCIÓN DEL PROYECTO
6 ETAPAS Y ACCIONES DEL PROYECTO.
7 MOVIMIENTOS DE SUELO PREVISTOS
8 DESCRIPCIÓN DEL ENTORNO INMEDIATO
9 DETERMINACION DEL AREA DE AFECTACION DIRECTA E INDIRECTA
IV. DESCRIPCION Y ANALISIS DEL MEDIO NATURAL Y SOCIOECONOMICO
1 MAPAS E INFORMACION GRÁFICA
2 MEDIO INERTE.
3 PLANIALTIMETRÍA.
4 ESTUDIO DE SUELOS E HIDROLOGÍA SUPERFICIAL Y SUBTERRÁNEA
5 MEDIO BIOTICO
6 MEDIO PERCEPTUAL
7 MEDIO SOCIOECONOMICO
8 ANÁLISIS DE ACEPTABILIDAD SOCIAL
V. ASPECTOS URBANISTICOS
1 DIRECTRICES URBANISTICAS DE LA ZONA Indicadores. Usos de Suelo. Sistema de movilidad urbana
2 EQUIPAMIENTO EXISTENTE Equipamiento Social. Salud. Educación. Seguridad. Administración. Comercios y Servicios
3 COBERTURA DE SERVICIOS E INFRAESTRUCTURA Energía eléctrica. Gas natural. Cloacas. Agua Potable. Asfalto. Desagües. Comunicaciones
4 SITUACION URBANA ACTUAL
V. EVALUACIÓN DE LOS IMPACTOS Y EFECTOS AMBIENTALES
1 MAPA DE RIESGOS AMBIENTALES NATURALES Y ANTRÓPICOS
2 ACCIONES DEL PROYECTO QUE PRODUCEN IMPACTO AMBIENTAL
3 FACTORES AMBIENTALES AFECTADOS
4 MATRIZ DE IMPACTOS AMBIENTALES
5 VALORACION DE IMPACTOS AMBIENTALES
6 ANALISIS DE LOS IMPACTOS EN EL SUBSISTEMA SOCIOECONÓMICO
7 ANÁLISIS DE LOS IMPACTOS EN EL SUBSITEMA EQUIPAMIENTOS E INFRAESTRUCTURA
VI. PLAN DE GESTION AMBIENTAL
1 PLAN DE GESTION AMBIENTAL DE LA ETAPA CONSTRUCTIVA
2 PLAN DE GESTION AMBIENTAL DE LA ETAPA DE FUNCIONAMIENTO
3 OBRAS DE MITIGACION AMBIENTAL
4 TRATAMIENTO DE RIESGOS AMBIENTALES
5 PROGRAMAS DE MONITOREO Y VIGILANCIA AMBIENTAL

VII. REFERENCIAS

1 BIBLIOGRAFIA CONSULTADA

2 NORMATIVA APLICABLE NACIONAL, PROVINCIAL, MUNICIPAL.

CAPÍTULO III

ZONAS URBANAS – PARÁMETROS URBANÍSTICOS

ZONA RESIDENCIAL 1 ESPECIAL (R 1E)	
Carácter:	
Zona de equipamiento administrativo, comercial y financiero de escala urbana, permitiéndose el uso de vivienda colectiva con estacionamiento propio.	
Usos:	
Ver planilla de Usos de Suelo. Usos de suelo principales: residencial, comercial.	
Delimitación:	
Lotes frentistas a Plaza San Martín y predio del Parque Central.	
Estructura edilicia:	
Se permiten edificios en altura entre medianeras, con actividad comercial en planta baja, viviendas y oficinas en pisos superiores.	
Subdivisión:	Superficies edificables:
Frente mínimo: 12 mts. Superficie mínima: 360 mts.2 Relación frente - fondo: 1:1 a 1:3	FOS: 0,80 FOT: 4
Módulos de estacionamiento:	Densidad habitacional:
1 módulo de 15 mts.2 por vivienda 1 módulo de 15 mts.2 cada 100 mts.2 construidos	1.000 hab. /ha.
Altura máxima:	Retiros:
17 mts. (Planta baja + 4 niveles)	No retiros obligatorios
Infraestructura requerida:	
Todos los servicios obligatorios: alumbrado público, agua corriente, energía eléctrica, gas natural, cloacas.	
Consideraciones especiales:	
En caso de establecer un retiro de frente el mismo será de 6 mts. como mínimo, debiendo materializarse una falsa fachada sobre línea municipal.	

ZONA RESIDENCIAL 1 (R 1)

Carácter:	
Zona destinada a equipamiento administrativo, comercial y financiero de escala urbana y viviendas unifamiliares y colectivas con usos complementarios a las mismas.	
Usos:	
Ver planilla de Usos de Suelo.	
Delimitación:	
Ver plano de zonificación. Usos de suelo principales: residencial, comercial.	
Estructura edilicia:	
Se permiten edificios en altura entre medianeras, con actividad comercial en planta baja, viviendas y oficinas en pisos superiores.	
Subdivisión:	Superficies edificables:
Frente mínimo: 12 mts. Superficie mínima: 360 mts.2 Relación frente - fondo: 1:1 a 1:3	FOS: 0,70 FOT: 1,8
Módulos de estacionamiento:	Densidad habitacional:
1 módulo de 15 mts.2 por vivienda 1 módulo de 15 mts.2 cada 100 mts.2 construidos	800 hab./ha.
Altura máxima:	Retiros:
14 mts. (Planta baja + 3 niveles)	De frente: 6 mts. mínimo (no obligatorio) Laterales: 3 mts. mínimo (no obligatorio) Fondo: 6 mts. mínimo (en manzanas cuadráticas de 80 mts. de lado mínimo)
Lotes en esquina:	
Adopta todos los parámetros de R1, pero el FOS es de 0,75 por tener doble ventilación a dos líneas municipales.	
Infraestructura requerida:	
Todos los servicios obligatorios: agua corriente, energía eléctrica, gas natural, cloacas.	
Consideraciones especiales:	
En caso de establecer un retiro de frente el mismo será de 6 mts. como mínimo, debiendo materializarse una falsa fachada sobre línea municipal.	

ZONA RESIDENCIAL 2 (R 2)

Carácter:	
Zona destinada a uso residencial con viviendas unifamiliares y colectivas, en la que se permiten usos complementarios compatibles al uso principal.	
Usos:	
Ver planilla de Usos de Suelo. Usos de suelo principales: residencial.	
Delimitación:	
Ver plano de zonificación.	
Estructura edilicia:	
Viviendas en planta baja y una planta alta, entre medianeras con retiro de frente.	
Subdivisión:	Superficies edificables:
Frente mínimo: 12 mts. Superficie mínima: 360 mts.2 Relación frente - fondo: 1:1 a 1:3	FOS: 0,60 FOT: 0,80
Módulos de estacionamiento:	Densidad habitacional:
1 módulo de 15 mts.2 por vivienda 1 módulo de 15 mts.2 cada 100 mts.2 construidos	280 hab./ha.
Altura máxima:	Retiros:
8 mts. (Planta baja + 1 nivel)	De frente: 3 mts. mínimo (*) Laterales: 3 mts. mínimo (no obligatorio)
Consideraciones especiales:	
Polígono Centro: (*) Dentro del polígono urbano establecido entre las calles Buratovich (al Norte), Roca (Oeste), Santa Cruz (Sur) Riavitz, Santa Fe norte, Lainez, y Av. San Martín (al Este), el retiro de frente NO es considerado obligatorio.	
Infraestructura requerida:	
Todos los servicios obligatorios: agua corriente, energía eléctrica, gas natural, cloacas.	

ZONA RESIDENCIAL 2 PERIURBANO (R 2P)

Carácter:	
Zona destinada a uso residencial con viviendas unifamiliares de baja densidad y semiperímetro libre. Son admitidos usos complementarios al uso residencial predominante. Se admite la construcción de solo una vivienda familiar por lote	
Usos:	
Ver planilla de Usos de Suelo. Usos de suelo principales: residencial.	
Delimitación:	
Ver plano de zonificación.	
Estructura edilicia:	
Una vivienda por lote con semiperimetro libre.	
Subdivisión:	Superficies edificables:
Frente mínimo: 12 mts. Superficie mínima: 360 mts.2 Relación frente - fondo: 1:1 a 1:3	FOS: 0,50 FOT: 0,60
Módulos de estacionamiento:	Densidad habitacional:
1 módulo de 15 mts.2	150 hab./ha.
Altura máxima:	Retiros:
8 mts. (Planta baja + 1 nivel)	De frente: 3 mts. mínimo (obligatorio) Laterales: 3 mts. mínimo (obligatorio) Fondo: 3 mts. mínimo (en manzanas cuadráticas de 80 mts. de lado mínimo)
Infraestructura requerida:	
Agua corriente, energía eléctrica, alumbrado público, gas natural, enripiado de calles, cordón cuneta. Cloacas: será exigible donde exista factibilidad.	

ZONA RESIDENCIAL 3 (R 3)

Carácter:	
Zona destinada a uso residencial de densidad atenuada. Son admitidos usos complementarios al uso residencial predominante.	
Usos:	
Ver planilla de Usos de Suelo. Usos de suelo principales: residencial.	
Delimitación:	
Ver plano de zonificación.	
Estructura edilicia:	
Viviendas de planta baja y un piso, con semiperímetro libre.	
Subdivisión:	Superficies edificables:
Frente mínimo: 15 mts. Superficie mínima: 450 mts.2 Relación frente - fondo: 1:1 a 1:3	FOS: 0,50 FOT: 0,60
Módulos de estacionamiento:	Densidad habitacional:
1 módulo de 15 mts.2 por vivienda 1 módulo de 15 mts.2 cada 100 mts.2 construidos	120 hab./ha.
Altura máxima:	Retiros:
8 mts. (Planta baja + 1 nivel)	De frente: 4 mts. mínimo Lateral: 3 mts. mínimo (obligatorio) Fondo: 3 mts. mínimo (en manzanas cuadráticas de 80 mts. de lado mínimo)
Infraestructura requerida:	
Agua corriente, energía eléctrica, alumbrado público, gas natural, enripiado de calles, cordón cuneta. Cloacas: será exigible donde exista factibilidad.	

ZONA RESIDENCIAL 4 (R 4)

Carácter:	
Zona destinada exclusivamente a uso residencial. Una unidad funcional por lote.	
Usos:	
Ver planilla de Usos de Suelo. Usos de suelo principales: residencial.	
Delimitación:	
Ver plano de zonificación.	
Estructura edilicia:	
Viviendas unifamiliares de baja densidad y perímetro libre.	
Subdivisión:	Superficies edificables:
Frente mínimo: 20 mts. Superficie mínima: 750 mts.2 Relación frente - fondo: 1:1 a 1:3	FOS: 0,20 FOT: 0,20
Módulos de estacionamiento:	Densidad habitacional:
1 módulo de 15 mts.2 por vivienda 1 módulo de 15 mts.2 cada 100 mts.2 construidos	40 hab./ha.
Altura máxima:	Retiros:
8 mts. (Planta baja + 1 nivel)	De frente: 6 mts. mínimo Lateral: 3 mts. mínimo Fondo: 3 mts. mínimo
Infraestructura requerida:	
Agua corriente, energía eléctrica, alumbrado público, gas natural, enripiado de calles, cordón cuneta. Cloacas: será exigible donde exista factibilidad.	

ZONA RESIDENCIAL DE BAJA DENSIDAD (RDB)	
Carácter:	
Zona destinada exclusivamente a uso residencial de baja densidad. Una unidad funcional por lote.	
Usos:	
Ver planilla de Usos de Suelo. Usos de suelo principales: residencial.	
Delimitación:	
Ver plano de zonificación.	
Estructura edilicia:	
Construcciones de perímetro libre. Admite club de campo o barrio cerrado (ver ordenanza)	
Subdivisión:	Superficies edificables:
Frente mínimo: 35 mts. Superficie mínima: 900 mts.2 Relación frente - fondo: 1:1 a 1:3	FOS: 0,25 FOT: 0,15
Módulos de estacionamiento:	Densidad habitacional:
2 módulos de 15 mts.2 por lote.	35 hab./ha.
Altura máxima:	Retiros:
8 mts. (Planta baja + 1 nivel)	De frente: 6 mts. mínimo Lateral: 4 mts. Mínimo Fondo: 4 mts. Mínimo
Infraestructura requerida:	
Agua corriente, energía eléctrica, alumbrado público, gas natural, enripiado de calles, cordón cuneta. Cloacas: será exigible donde exista factibilidad.	

ZONA RESIDENCIAL ESPECIAL ORD. N°3.257/11
Carácter:
Zona regida por los parámetros urbanísticos definidos en la Ordenanza N° 3.257/11. En cuanto al parámetro urbanístico "densidad" se aplicará lo establecido en la Ordenanza N° 2.507/06, debido a que dicho parámetro no está definido en la Ordenanza N° 3.257/11.

CORREDORES URBANOS – PARÁMETROS URBANÍSTICOS

CORREDOR COMERCIAL CENTRO (CCC)
Carácter:
Corredor predominantemente comercial, admite el uso residencial.
Usos:
Ver planilla de Usos de Suelo. Usos de suelo principales: comercial.
Parámetros Urbanísticos:
Adoptará los parámetros urbanísticos de R1. En el sectorcomprendido por la zona R1 Especial, tomará las características de dicha zona, y en el tramo que atraviese la zona R2 adoptará los parámetros de corredor CR 2E.
Consideraciones especiales:
En caso de establecer un retiro de frente el mismo será de 6 mts. como mínimo, debiendo materializarse una falsa fachada sobre línea municipal.

CORREDOR COMERCIAL NORTE (CCN)
Carácter:
Corredor predominantemente comercial, admite el uso residencial.
Usos:
Ver planilla de Usos de Suelo. Usos de suelo principales: comercial.
Parámetros Urbanísticos:
Adoptará los parámetros urbanisticos de CER2
Consideraciones especiales:
Retiro Lateral: 3 mts. (no obligatorio) Retiro de frente: 3 mts. (no obligatorio).

CORREDOR COMERCIAL MULTITROCHA (CCM)
Carácter:
Corredor predominantemente comercial, admite el uso residencial.
Usos:
Ver planilla de Usos de Suelo. Usos de suelo principales: comercial.
Parámetros Urbanísticos:
Adoptará los parámetros urbanísticos de la zona R1.
El tramo Oeste definido entre las calles Zabaleta y Batilana (alsur) / Libertad (al Norte) y el tramo Este definido entre las calles Riavitz y Lugones (al sur) / 25 de Mayo (al norte) adoptará los usos de suelo propios del corredor mixto oeste.
Consideraciones especiales:
En caso de establecer un retiro de frente el mismo será de 6 mts. como mínimo, debiendo materializarse una falsa fachada sobre línea municipal.

CORREDOR COMERCIAL SUR (CCS)
Carácter:
Corredor predominantemente comercial, admite el uso residencial.
Usos:
Ver planilla de Usos de Suelo. Usos de suelo principales: comercial.
Parámetros Urbanísticos:
Adoptará los parámetros urbanísticos del Corredor CR 2E
Consideraciones especiales:
Retiro Lateral: 3 mts. (no obligatorio) Retiro de frente: 3 mts. (no obligatorio).

CORREDOR COMERCIAL ESTE (CCE)
Carácter:
Corredor predominantemente comercial, admite el uso residencial.
Usos:
Ver planilla de Usos de Suelo. Usos de suelo principales: comercial.
Parámetros Urbanísticos:
Adoptará los parámetros urbanísticos de la zona R2.

CORREDOR DE EQUIPAMIENTO URBANO (CEU)
Carácter:
Corredor donde predominan los usos comerciales y servicios relacionados con el sistema de salud. Admite el uso residencial.
Usos:
Ver planilla de Usos de Suelo. Usos de suelo principales: comercial, servicios de salud, administración.
Parámetros Urbanísticos:
Adoptará los parámetros urbanísticos del Corredor C R2E
Consideraciones especiales:
Retiro Lateral: 3 mts. (no obligatorio) Retiro de frente: 3 mts. (no obligatorio).

CORREDOR MIXTO NORTE (CMN)
Carácter:
Corredor de servicios urbanos y comercios. Admite el uso residencial
Usos:
Ver planilla de Usos de Suelo. Usos de suelo principales: comercial, servicios.
Parámetros Urbanísticos:
Conservará los parámetros urbanísticos de la zona R2, admitiéndose mayor diversidad de usos de suelo (ver planilla).

CORREDOR MIXTO OESTE (CMO)
Carácter:
Corredor de servicios urbanos y comercios. Admite el uso residencial
Usos:
Ver planilla de Usos de Suelo. Usos de suelo principales: comercial, servicios.
Parámetros Urbanísticos:
Adoptará los parámetros urbanisticos del CR 2E hasta el cruce de la calle Roca y Buratovich, y hacia el norte parámetros urbanísticos de R2.

CORREDOR MIXTO NORESTE (CMNE)
Carácter:
Corredor de servicios urbanos y comercios. Admite el uso residencial
Usos:
Ver planilla de Usos de Suelo. Usos de suelo principales: comercial, servicios.
Parámetros Urbanísticos:
Adoptará los parámetros urbanísticos de la zona R2.
Consideraciones especiales:
El tramo del corredor situado sobre la calle Río Colorado, admitirá los usos del Corredor de Servicios Norte (CSN). Los tramos del corredor situados sobre Av. del Trabajo, que atraviesen sectores ya urbanizados, adoptarán únicamente los usos permitidos en el Corredor Comercial Este (CCE).

CORREDOR MIXTO ESTE (CME)
Carácter:
Corredor de servicios urbanos y comercios. Admite el uso residencial
Usos:
Ver planilla de Usos de Suelo. Usos de suelo principales: comercial, servicios.
Parámetros Urbanísticos:
Conservará los parámetros urbanísticos de la zona R2, admitiéndose mayor diversidad de usos de suelo (ver planilla).

CORREDOR DE EQUIPAMIENTO Y SERVICIOS (CES)
Carácter:
Equipamiento y servicios orientados principalmente al turismo y el esparcimiento. Se permite el uso residencial.
Usos:
Ver planilla de Usos de Suelo. Usos de suelo principales: comercial, servicios turísticos y esparcimiento.
Parámetros Urbanísticos:
Para usos no residenciales: Superficie mínima: 1/2 hectárea. FOS: 0,3 FOT: 0,5 Altura máx: 11 mts. (PLANTA BAJA + 2 NIVELES) Para usos residenciales: se regirán con los parámetros urbanísticos de las zonas aledañas al corredor.

CORREDOR DE SERVICIOS NORTE (CSN)
Carácter:
Corredor exclusivo de equipamiento y servicios. El uso residenciales complementario. El uso comercial tiene carácter condicionado.
Usos:
Ver planilla de Usos de Suelo. Usos de suelo principales: servicios urbanos.
Parámetros Urbanísticos:
Superficie mínima: 500 mts. Frente mínimo: 20 mts. FOS: 0,6 FOT: 0,8 Altura máxima: 11 mts. (Planta baja + 2 niveles)

SERVICIO DE RUTA URBANO (SRU)
Carácter:
Se materializa en los lotes frentistas a calles colectoras de laRuta Nacional 22 en los sectores indicados en el plano de Corredores Urbanos. Corredor exclusivo de equipamiento y servicios. El uso residencial es complementario. El uso comercial tiene carácter condicionado.
Usos:
Ver planilla de usos de suelo. Usos de suelo principales: servicios urbanos.
Parámetros Urbanísticos:
Superficie mínima: 500 mts. Frente mínimo: 20 mts. FOS: 0,6 FOT: 0,8 Altura máxima: 11 mts. (Planta baja + 2 niveles)

CORREDOR RESIDENCIAL 2 ESPECIAL (CR 2E)

Carácter:	
Corredor destinado al uso residencial y comercial, con viviendas unifamiliares y colectivas.	
Usos:	
Se aplican los usos de de suelo correspondientes a la zona o orredor donde se refiera.	
Estructura edilicia:	
Se permite planta baja y dos pisos entre medianeras, con la posibilidad de actividad comercial en planta baja y/o viviendas y oficinas en pisos superiores.	
Subdivisión:	Superficies edificables:
Frente mínimo: 12 mts. Superficie mínima: 360 mts.2 Relación frente - fondo: 1:1 a 1:3	FOS: 0,70 FOT: 1,4
Módulos de estacionamiento:	Densidad habitacional:
1 módulo de 15 mts.2 por vivienda 1 módulo de 15 mts.2 cada 100 mts.2 construidos	500 hab./ha.
Altura máxima:	
11 mts. (Planta baja + 2 niveles)	
Infraestructura requerida:	
Todos los servicios obligatorios: agua corriente, energía eléctrica, gas natural, alumbrado público, cloacas, cordón cuneta.	

CAPÍTULO IV

USOS DE SUELO - ZONA RURAL Y EXTRAURBANA

Las zonas consideradas en este capítulo se encuentran dentro de sectores no urbanos del ejido. Estos sectores poseen diferente carácter de acuerdo al uso de suelo predominante, y requieren de un análisis diferente al aplicado en las zonas urbanas.
La presente actualización, se realizó considerando las variaciones experimentadas desde el año 2.004 a la fecha, lo cual requirió modificaciones tanto en la configuración de las zonas, como en el listado de categorías de usos y actividades contempladas.

A continuación se presenta la descripción de las distintas zonas, las superficies mínimas de subdivisión previstas para cada caso, además de consideraciones particulares. En cuanto a los usos de suelo permitidos en las distintas zonas, se encuentran en el "Cuadro de Usos de Suelo – Zona Rural y Extraurbana" que figura en el anexo del presente capítulo.

ZR 1: MESETAS Y PIE DE BARDA	
UBICACIÓN:	Ver plano de zonificación rural.
USO PRINCIPAL:	Actividad Hidrocarburífera
SUPERFICIE MINIMA DE SUBDIVISIÓN:	10 Has.
CONSIDERACIONES PARTICULARES:	Las actividades deben evitar los cañadones y otras zonas de alta sensibilidad geomorfológico.

ZR 2: FRENTE DE BARDAS	
UBICACIÓN:	Todos los sectores comprendidos por el área que se inicia a 100 metros desde la ruptura de pendiente hacia la meseta, la escarpa y la zona de taludes.
USO PRINCIPAL:	Área de protección especial.
SUPERFICIE MINIMA DE SUBDIVISIÓN:	No se permiten fraccionamientos.
CONSIDERACIIONES PARTICULARES:	A los efectos del uso del suelo esta zona toma las características de "área protegida", con el objeto de preservar el paisaje y evitar la aceleración de procesos erosivos, la degradación de suelos y vegetación.

ZR 3: COLONIA SAN FRANCISCO	
UBICACIÓN:	Ver plano de zonificación rural.
USO PRINCIPAL:	Agricultura, actividades agropecuarias.
SUPERFICIE MINIMA DE SUBDIVISIÓN:	10 has.

ZR 4: SERVICIO DE RUTA EXTRAURBANO	
UBICACIÓN:	Comprende los lotes frentistas a la Ruta Nacional22, en la zona indicada en plano. Se extiende en una franja de 200 metros hacia el interior de los lotes, desde la línea municipal.
USO PRINCIPAL:	Servicios al transporte
SUPERFICIE MINIMA DE SUBDIVISIÓN:	1/2 Hectárea. Frente mínimo: 80 mts.
CONSIDERACIONES PARTICULARES:	- En las parcelas que excedan la franja de servicios, el uso de suelo en la superficie excedente se regirá por lo dispuesto en la zona que la comprende, según el plano de zonificación. - Debido a la variabilidad de usos que admite la zona, el uso de suelo propuesto deberá demostrar la compatibilidad con los usos instalados en el entorno.

ZR 5: CHINA MUERTA	
UBICACIÓN:	Ver plano de zonificación rural.
USO PRINCIPAL:	Agricultura, actividades agropecuarias
SUPERFICIE MINIMA DE SUBDIVISIÓN:	3 has.

ZR 6: ZONA AGROPRODUCTIVA OESTE	
UBICACIÓN:	Ver plano de zonificación rural.
USO PRINCIPAL:	Agricultura, actividades agropecuarias
SUPERFICIE MINIMA DE SUBDIVISIÓN:	10 has.

ZR 7: ZONA AGROPRODUCTIVA CENTRO	
UBICACIÓN:	Ver plano de zonificación rural.
USO PRINCIPAL:	Agricultura, actividades agropecuarias
SUPERFICIE MINIMA DE SUBDIVISIÓN:	10 has.

ZR 8: ZONA RURAL DE TRANSICIÓN	
Ubicación:	Ver plano de zonificación rural.
Uso principal:	Agricultura
SUPERFICIE MINIMA DE SUBDIVISIÓN:	3 has.
CONSIDERACIONES PARTICULARES:	Toda actividad a radicarse en la zona, debe preservar la configuración original del oasis de riego, evitándose la eliminación de canales de riego y alamedas perimetrales, según lo estipulado en el Capítulo I "Disposiciones Generales".

ZR 9: ZONA RIBEREÑA E ISLAS	
UBICACIÓN:	Ver plano de zonificación rural.
USO PRINCIPAL:	Agricultura, turismo.
SUPERFICIE MINIMA DE SUBDIVISIÓN:	Para uso de suelo agricultura: 10 has. Para otros usos de suelo: Se determinará de acuerdo al proyecto presentado.
CONSIDERACIONES PARTICULARES:	La zona admite el uso residencial de carácter no permanente; los proyectos deberán someterse previamente al procedimiento EIA y se regirán en función de los siguientes parámetros urbanísticos: - Superficie mínima de parcela: 1.000 mts.2. - FOS: 0,20 - FOT: 0,35 - Densidad: 1 vivienda por lote - Altura máxima: 8 mts. (planta baja + 1 nivel) No se permiten urbanizaciones cerradas.
	Toda la zona tiene el carácter de área de protección especial, debiendo garantizarse la preservación de los atributos paisajísticos y ecológicos existentes.
	Todo uso de suelo deberá verificar previamente la línea de ribera, y solicitar la correspondiente autorización por parte del organismo provincial competente.

ZR 10: ZONA MIXTA NORESTE	
UBICACIÓN:	Ver plano de zonificación rural.
USO PRINCIPAL:	Servicios industriales.
SUPERFICIE MINIMA DE SUBDIVISIÓN:	1/4 de hectárea. Frente mínimo: 50 metros
CONSIDERACIONES PARTICULARES:	Debido a la variabilidad de usos que admite la zona, el uso de suelo propuesto deberá demostrar la compatibilidad con los usos instalados en el entorno.

ZR 11: ZONA INDUSTRIAL	
UBICACIÓN:	Ver plano de zonificación rural.
USO PRINCIPAL:	Industria
SUPERFICIE MINIMA DE SUBDIVISIÓN:	1/4 de hectárea Frente mínimo: 50 metros
CONSIDERACIONES PARTICULARES:	El ordenamiento de los usos de suelo en el sector comprendido por el Parque Industrial, se regirá de acuerdo a las disposiciones fijadas en dicha zona por la normativa municipal vigente.

CORREDORES DE VINCULACION URBANO RURAL	
UBICACIÓN:	Corredores definidos dentro de la zona rural, en espacios aledaños a la Ruta Nac. 22, vías férreas, canal principal de riego y caminos rurales importantes. Ver plano.
CONSIDERACIONES PARTICULARES:	El análisis de factibilidad territorial ambiental de usos de suelo que se propongan en estos corredores, se realizará considerando las potencialidades y restricciones de cada corredor. En todos los casos se realizará una evaluación ambiental previa. En los proyectos cuya complejidad lo amerite, la autoridad municipal aplicará el procedimiento EIA. En tramos en los que el corredor ingrese a zonas urbanas, los usos de suelo se regirán por los parámetros establecidos para dichas zonas.